CLASSE 2

Tarifs applicables au 1er février 2025

A7 A8 A9 A46 A54 A709

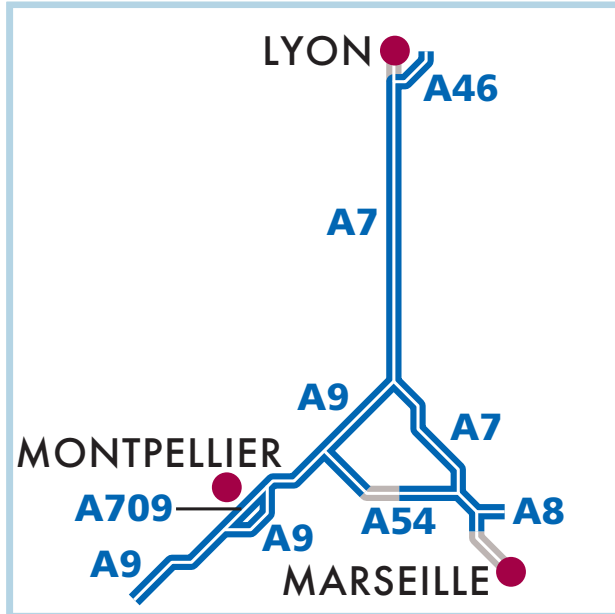

Lyon

	Bifurcation A46S/A43 vers A43 ou A46	(11) Fort de St-Priest	(12) St-Priest centre	(13) Mions	(14) Vénissieux	(15) Marennes	(16) Communay	Bifurcation A46S/A7/A47 vers Lyon ou St-Etienne	(8) Chasse sud	(9) Vienne nord	(10) Condrieu	(11) Vienne sud	Péage de Vienne	(11.1) Auberives (accès nord/sud uniquement)	(12) Chanas	(13) Tain	(14) Valence nord	(15) Valence sud	(16) Loriol	(17) Montélimar nord	(18) Montélimar sud	(19) Bollène	(20) Orange nord	(21) Orange centre	(22) Orange sud	(23) Avignon nord	(24) Avignon sud	(25) Cavaillon	(26) Sénas	(27) Salon nord	(15) Salon sud	(14) Grans	(13) Salon ouest	Péage de St-Martin-de-Crau	(12) St-Martin-de-Crau est	Péage de Lançon (Aix/Berre)	(28) Rognac Berre	(28) Coudoux	(29) Aix ouest	(22) Roquemaure	(23) Remoulins	(24) Nîmes est	(25) Nîmes ouest	(1) Nîmes centre	(2) Nîmes Garons	Péage d'Arles	(26) Gallargues	(27) Lunel	Péage de Baillargues	(28) Vendargues	(29) Montpellier est	(30) Montpellier sud	(31) Montpellier ouest
(11) Fort de St-Priest	0																																																				
(12) St-Priest centre	0	.																																																			
(13) Mions	0	.	0																																																		
(14) Vénissieux	0	.	0	0																																																	
(15) Marennes	0	.	0	0	0																																																
(16) Communay	0	.	0	0	0	0																																															
Bifurcation A46S/A7/A47 vers Lyon ou St-Etienne	0	.	0	0	0	0	0																																														
(8) Chasse sud	.	.	.	.	.	.	.	.																																													
(9) Vienne nord	0	.	0	0	0	0	0	0	.																																												
(10) Condrieu	1,1	.	1,1	1,1	1,1	1,1	1,1	1,1	1,1	.																																											
(11) Vienne sud	2,5	.	2,5	2,5	2,5	2,5	2,5	2,5	2,5	.	2,5																																										
Péage de Vienne	.	.	.	.	.	.	.	.	.	.	.	.																																									
(11.1) Auberives	.	.	.	.	.	.	.	.	.	.	.	.	.																																								
(12) Chanas	7,3	.	7,3	7,3	7,3	7,3	7,3	7,3	7,3	.	.	7,3	7,3	1,2																																							
(13) Tain	11	.	11	11	11	11	11	11	11	.	.	11	11	4,3	4,1																																						
(14) Valence nord	14,4	.	14,4	14,4	14,4	14,4	14,4	14,4	14,4	.	.	14,4	14,4	7,2	5,7	1,6																																					
(15) Valence sud	14,6	.	14,6	14,6	14,6	14,6	14,6	14,6	14,6	.	.	14,6	14,6	7,6	6,5	2,5	1																																				
(16) Loriol	19,1	.	19,1	19,1	19,1	19,1	19,1	19,1	19,1	.	.	19,1	19,1	11	10	5,9	3,4	2,9																																			
(17) Montélimar nord	21,2	.	21,2	21,2	21,2	21,2	21,2	21,2	21,2	.	.	21,2	21,2	13,8	11,5	7,3	4,6	4	1,1																																		
(18) Montélimar sud	25,1	.	25,1	25,1	25,1	25,1	25,1	25,1	25,1	.	.	25,1	25,1	16,8	15,3	11,3	8,2	7,9	4,9	3																																	
(19) Bollène	27,4	.	27,4	27,4	27,4	27,4	27,4	27,4	27,4	.	.	27,4	27,4	19,1	17,8	13,7	10,6	10,3	7,4	5,4	3,1																																
(20) Orange nord	.	.	.	.	.	.	.	.	.	.	.	.	.	.	.	.	.	.	.	.	.	.																															
(21) Orange centre	31,3	.	31,3	31,3	31,3	31,3	31,3	31,3	31,3	.	.	31,3	31,3	23,1	21,4	17,4	14,5	14,2	11,1	8,6	5,1	3,1	0,8																														
(22) Orange sud	33	.	33	33	33	33	33	33	33	.	.	33	33	24	23,4	19	17,3	17,1	13,7	10,8	6	4	1,4	0,6																													
(23) Avignon nord	35,7	.	35,7	35,7	35,7	35,7	35,7	35,7	35,7	.	.	35,7	35,7	27,7	26,2	21,8	19,8	19,6	16	13,5	8,8	6,2	3,6	3,1	2,6																												
(24) Avignon sud	36,4	.	36,4	36,4	36,4	36,4	36,4	36,4	36,4	.	.	36,4	36,4	29,1	27,9	23,3	21,3	21,1	16,8	14,9	10,7	8,4	4,4	4,3	4,1	1,2																											
(25) Cavaillon	37,2	.	37,2	37,2	37,2	37,2	37,2	37,2	37,2	.	.	37,2	37,2	30,6	28,1	23,8	22,1	21,9	18,2	15,7	11,4	9,3	6	5,5	4,9	3,4	1,5																										
(26) Sénas	42,4	.	42,4	42,4	42,4	42,4	42,4	42,4	42,4	.	.	42,4	42,4	34,2	33	28,6	25,5	25,3	22	19,4	15	12,9	8,7	8,5	8,4	5,3	3,6	1,4																									
(27) Salon nord	42,8	.	42,8	42,8	42,8	42,8	42,8	42,8	42,8	.	.	42,8	42,8	34,6	33,5	29	26,7	26,4	22,3	20,8	15,9	14,5	9,6	9,1	8,6	6,1	4,7	2,6	0,8																								
(15) Salon sud	43	.	43	43	43	43	43	43	43	.	.	43	43	35,1	33,9	29,4	27,3	27,1	23,3	21,6	16,7	15,1	10,6	10,2	10	7,4	5,4	3,7	1,9	.																							
(14) Grans	43,2	.	43,2	43,2	43,2	43,2	43,2	43,2	43,2	.	.	43,2	43,2	35,3	34,1	29,6	27,5	27,3	23,5	21,8	16,9	15,3	10,8	10,4	10,2	7,6	5,6	3,9	2,3	.	.																						
(13) Salon ouest	45,5	.	45,5	45,5	45,5	45,5	45,5	45,5	45,5	.	.	45,5	45,5	37,7	36,3	32	29,6	29,4	26,3	23,1	19	17,3	12,6	12,4	12,2	9,3	8	5,1	3,5	.	.	0,7																					
Péage de St-Martin-de-Crau	46,1	.	46,1	46,1	46,1	46,1	46,1	46,1	46,1	.	.	46,1	46,1	39	38,1	33,7	31,4	31,2	27,2	25,8	21	19,2	14,6	14,2	14	11,5	9,8	7,9	5,4	.	.	3,7	2,3																				
(12) St-Martin-de-Crau est	46,1	.	46,1	46,1	46,1	46,1	46,1	46,1	46,1	.	.	46,1	46,1	39	38,1	33,7	31,4	31,2	27,2	25,8	21	19,2	14,6	14,2	14	11,5	9,8	7,9	5,4	.	.	3,7	2,3	.																			
Péage de Lançon (Aix/Berre)	45,7	.	45,7	45,7	45,7	45,7	45,7	45,7	45,7	.	.	45,7	45,7	39,4	36,9	32,1	30,6	30,4	25,9	24,3	20,2	18,1	14,3	14	13,8	11,6	9,8	7,9	4,8	.	3	3,6	6	7,4	7,4																		
(28) Rognac Berre	45,7	.	45,7	45,7	45,7	45,7	45,7	45,7	45,7	.	.	45,7	45,7	39,4	36,9	32,1	30,6	30,4	25,9	24,3	20,2	18,1	14,3	14	13,8	11,6	9,8	7,9	4,8	.	3	3,6	6	7,4	7,4	.																	
(28) Coudoux	.	.	.	.	.	.	.	.	.	.	.	.	.	.	.	.	.	.	.	.	.	.	.	.	.	.	.	.	.	.	.	.	.	.	.	.	.																
(29) Aix ouest	45,7	.	45,7	45,7	45,7	45,7	45,7	45,7	45,7	.	.	45,7	45,7	39,4	36,9	32,1	30,6	30,4	25,9	24,3	20,2	18,1	14,3	14	13,8	11,6	9,8	7,9	4,8	.	3	3,6	6	7,4	7,4	.	3,2	3,2															
(22) Roquemaure	35,5	.	35,5	35,5	35,5	35,5	35,5	35,5	35,5	.	.	35,5	35,5	27,1	25,9	21,6	18,7	18,4	14,7	13	7,5	5	2,3	2,2	.	.	.	.	.	.	.	.	.	.	.	.	.	.	.														
(23) Remoulins	36,9	.	36,9	36,9	36,9	36,9	36,9	36,9	36,9	.	.	36,9	36,9	28,7	27,3	23	20,2	20	16,3	14,6	10,1	7	3,8	3,6	.	.	.	.	.	.	.	.	.	.	.	.	.	.	.	1,9													
(24) Nîmes est	41,7	.	41,7	41,7	41,7	41,7	41,7	41,7	41,7	.	.	41,7	41,7	34	32,2	27,6	25,3	25	21,3	18,7	14	11,6	6,1	5,8	.	.	.	.	.	.	.	.	.	.	.	.	.	.	.	4,9	2,8												
(25) Nîmes ouest	42,1	.	42,1	42,1	42,1	42,1	42,1	42,1	42,1	.	.	42,1	42,1	34,4	32,6	28	25,9	25,6	22,3	19,4	14,9	12,8	8	7,5	.	.	.	.	.	.	.	.	.	.	.	.	.	.	.	5,6	4	0,9											
(1) Nîmes centre	42,2	.	42,2	42,2	42,2	42,2	42,2	42,2	42,2	.	.	42,2	42,2	34,6	32,8	28,1	26,1	25,8	22,5	19,6	15,1	13	8,9	7,6	.	.	.	.	.	.	.	.	.	.	.	.	.	.	.	5,7	4,1	1	0,4										
(2) Nîmes Garons	42,4	.	42,4	42,4	42,4	42,4	42,4	42,4	42,4	.	.	42,4	42,4	34,8	33,2	28,8	26,5	26,3	23	20,5	15,8	14,1	9,8	9,3	.	.	.	.	.	.	.	.	.	.	.	.	.	.	.	6,5	4,3	1,8	1,4	0,8									
Péage d'Arles	45	.	45	45	45	45	45	45	45	.	.	45	45	36,1	35,7	31,3	28,4	28,2	25	23,5	18	15,9	11,8	11,6	.	.	.	.	.	.	.	.	.	.	.	.	.	.	.	9,2	6	4	3,8	3,1	2,4								
(26) Gallargues	45	.	45	45	45	45	45	45	45	.	.	45	45	37,6	35,6	31,2	28,5	28,3	24,8	21,7	18	15,8	11,5	11,3	.	.	.	.	.	.	.	.	.	.	.	.	.	.	.	8,9	6,2	3,9	3	3,1	4,2	6,7							
(27) Lunel	45,4	.	45,4	45,4	45,4	45,4	45,4	45,4	45,4	.	.	45,4	45,4	38	36	31,6	28,9	28,7	25,2	22,3	18,4	16,3	12,3	11,9	.	.	.	.	.	.	.	.	.	.	.	.	.	.	.	9,2	6,8	4,4	3,6	3,8	4,7	7,2	0,8						
Péage de Baillargues	50,7	.	50,7	50,7	50,7	50,7	50,7	50,7	50,7	.	.	50,7	50,7	42,4	41,1	36,4	34,1	33,9	30,3	26,4	22,8	20,9	15	14,9	.	.	.	.	.	.	.	.	.	.	.	.	.	.	.	13,8	11,1	6,4	5,4	5,9	7,1	10,8	2,3	1,9					
(28) Vendargues	50,7	.	50,7	50,7	50,7	50,7	50,7	50,7	50,7	.	.	50,7	50,7	42,4	41,1	36,4	34,1	33,9	30,3	26,4	22,8	20,9	15	14,9	.	.	.	.	.	.	.	.	.	.	.	.	.	.	.	13,8	11,1	6,4	5,4	5,9	7,1	10,8	2,3	1,9	.				
(29) Montpellier est	50,7	.	50,7	50,7	50,7	50,7	50,7	50,7	50,7	.	.	50,7	50,7	42,4	41,1	36,4	34,1	33,9	30,3	26,4	22,8	20,9	15	14,9	.	.	.	.	.	.	.	.	.	.	.	.	.	.	.	13,8	11,1	6,4	5,4	5,9	7,1	10,8	2,3	1,9	.	0			
(30) Montpellier sud	50,7	.	50,7	50,7	50,7	50,7	50,7	50,7	50,7	.	.	50,7	50,7	42,4	41,1	36,4	34,1	33,9	30,3	26,4	22,8	20,9	15	14,9	.	.	.	.	.	.	.	.	.	.	.	.	.	.	.	13,8	11,1	6,4	5,4	5,9	7,1	10,8	2,3	1,9	.	0	0		
(31) Montpellier ouest	50,7	.	50,7	50,7	50,7	50,7	50,7	50,7	50,7	.	.	50,7	50,7	42,4	41,1	36,4	34,1	33,9	30,3	26,4	22,8	20,9	15	14,9	.	.	.	.	.	.	.	.	.	.	.	.	.	.	.	13,8	11,1	6,4	5,4	5,9	7,1	10,8	2,3	1,9	.	0	0	0	
(32) St-Jean-de-Vedas	50,7	.	50,7	50,7	50,7	50,7	50,7	50,7	50,7	.	.	50,7	50,7	42,4	41,1	36,4	34,1	33,9	30,3	26,4	22,8	20,9	15	14,9	.	.	.	.	.	.	.	.	.	.	.	.	.	.	.	13,8	11,1	6,4	5,4	5,9	7,1	10,8	2,3	1,9	.	0	0	0	0

Toulouse Espagne

CLASSE 2

Tarifs applicables au 1er février 2025

A7 A9 A46 A54 A61 A62 A66 A75

	Bifurcation A46S/A43 vers A43 ou A46	12 St-Priest centre	13 Mions	14 Vénissieux	15 Marennes	16 Communay	Bifurcation A46S/A7/A47 vers Lyon ou St-Étienne	8 Chasse sud	11 Vienne sud	Péage de Vienne	11.1 Auberives (accès nord/sud uniquement)	12 Chanas	13 Tain	14 Valence nord	15 Valence sud	16 Loriol	17 Montélimar nord	18 Montélimar sud	19 Ballène	20 Orange nord	21 Orange	22 Roquemaure	23 Remoulins	24 Nîmes est	25 Nîmes ouest	1 Nîmes centre	2 Nîmes Garons	Péage d'Arles	26 Gallargues	27 Lunel
A9 – 33 Sète	54,3	54,3	54,3	54,3	54,3	54,3	54,3	54,3	54,3	54,3	46,1	44,3	40,3	37,7	37,5	33,3	30,3	26,3	24,1	18,3	18,1	17	14,3	9,7	8,7	9,1	9,8	14	5,7	5,2
A9 – 34 Agde Pezenas	57,6	57,6	57,6	57,6	57,6	57,6	57,6	57,6	57,6	57,6	49,7	47,7	43,5	40,9	40,7	37	33,7	29,6	27,1	21,4	21,2	20,3	17,8	13	12,1	12,5	13,2	17,6	9	8,6
A75 Péage de Béziers-Cabrials	59,8	59,8	59,8	59,8	59,8	59,8	59,8	59,8	59,8	59,8	52,3	50,2	45,8	43,3	43	39,1	36,4	32,7	30,2	23,7	23,5	23	20,4	15,8	14,3	14,7	15,1	19,6	11	10,6
A9 – 36 Béziers ouest	60,6	60,6	60,6	60,6	60,6	60,6	60,6	60,6	60,6	60,6	53,2	51,1	46,7	44,2	43,9	40,4	37,3	33,6	31,1	25,1	24,8	23,9	21,3	17	15,6	16	16,7	20,9	12,6	12,1
A9 – 37 Narbonne est	65,9	65,9	65,9	65,9	65,9	65,9	65,9	65,9	65,9	65,9	57,8	56	51,9	49,1	48,9	45,3	42,3	38,1	35,9	29,8	29,6	28,2	26,2	21,7	20,7	21,1	21,6	26,3	17,4	17
A9 – 38 Narbonne sud	66,2	66,2	66,2	66,2	66,2	66,2	66,2	66,2	66,2	66,2	58	56,2	52,1	49,3	49,1	45,5	42,5	38,3	36,1	30	29,8	28,4	26,4	21,9	20,9	21,3	21,8	26,5	17,6	17,2
A9 – 39 Sigean	69,6	69,6	69,6	69,6	69,6	69,6	69,6	69,6	69,6	69,6	62,1	60,1	55,8	53	52,8	49,6	46,1	42,6	40,5	34	33,9	32,2	30,8	26,1	25	25,4	25,7	30,3	21,8	21,2
A9 – 40 Leucate	70,4	70,4	70,4	70,4	70,4	70,4	70,4	70,4	70,4	70,4	63,5	61,2	56,8	54,5	54,3	50,3	47,2	43,6	41,2	35,3	35,1	34	31,6	27,6	25,9	26,2	27,2	31,3	22,9	22,4
A9 – 41 Perpignan nord	76,1	76,1	76,1	76,1	76,1	76,1	76,1	76,1	76,1	76,1	69,2	67,1	62,9	60,5	60,1	56,3	53,4	49,5	47,2	40,5	40,4	39,3	38	33,1	32,1	32,5	33	37	28,6	28,2
A9 – 42 Perpignan sud	76,4	76,4	76,4	76,4	76,4	76,4	76,4	76,4	76,4	76,4	69,5	67,4	63,2	60,8	60,3	56,6	53,7	49,8	47,5	40,7	40,6	39,6	38,2	33,4	32,3	32,7	33,2	37,3	29	28,7
A9 – 43 Le Boulou (système fermé)	81,3	81,3	81,3	81,3	81,3	81,3	81,3	81,3	81,3	81,3	73,2	71,1	67,2	64,3	64,1	60,8	57,2	53,4	51,1	44,7	44,6	43,9	41,7	37,6	36,3	36,7	36,9	41,2	32,8	32,2
A9 – Péage du Perthus	84,1	84,1	84,1	84,1	84,1	84,1	84,1	84,1	84,1	84,1	78,3	76,2	71,8	68,3	67,7	65,3	61,9	58,1	55,8	48,5	48,3	47,9	45,9	41,8	40,4	40,6	41,5	45,8	37,1	36,5
A9 – Frontière Espagnole	84,1	84,1	84,1	84,1	84,1	84,1	84,1	84,1	84,1	84,1	78,3	76,2	71,8	68,3	67,7	65,3	61,9	58,1	55,8	48,5	48,3	47,9	45,9	41,8	40,4	40,6	41,5	45,8	37,1	36,5
A61 – 25 Lezignan	69,4	69,4	69,4	69,4	69,4	69,4	69,4	69,4	69,4	69,4	62	60	55,6	52,1	51,9	49,4	45,9	42,4	39,9	34,1	34	32,5	30,6	26,1	25	25,4	25,7	29,7	21,7	21
A61 – 24 Carcassonne est	75,3	75,3	75,3	75,3	75,3	75,3	75,3	75,3	75,3	75,3	67,9	65,5	61,3	58,5	58,3	55	52	48	45,7	39,3	39,2	38,5	36,5	31,9	31,1	31,5	31,7	36,4	27,5	27,1
A61 – 23 Carcassonne ouest	75,6	75,6	75,6	75,6	75,6	75,6	75,6	75,6	75,6	75,6	68,2	66	61,8	59,3	58,9	55,7	52,5	48,7	46,5	40	39,9	39,2	37,2	32,6	31,7	32,1	32,4	36,7	28,3	27,9
A61 – 22 Bram	79,2	79,2	79,2	79,2	79,2	79,2	79,2	79,2	79,2	79,2	71,5	69,7	65,4	63,3	62,9	59,9	56,8	53,2	50,8	44,9	44,8	43,3	41,1	37,3	36,2	36,6	37,3	41	32,5	32
A61 – 21 Castelnaudary	82,4	82,4	82,4	82,4	82,4	82,4	82,4	82,4	82,4	82,4	75,5	73,3	69	65,9	65,7	62,4	59,8	56,2	53,8	47	46,9	46,3	44,1	40,2	38,9	39,2	39,5	43,5	35,8	34,6
A61 – 20 Villefranche-de-Lauragais	85,9	85,9	85,9	85,9	85,9	85,9	85,9	85,9	85,9	85,9	78,2	76,4	71,7	69,5	69,3	65,7	62,7	58,8	56,3	50	49,9	48,2	47	43	41,8	42,2	42,9	46,5	38,4	37,9
A66 – 1 Nailloux	86,1	86,1	86,1	86,1	86,1	86,1	86,1	86,1	86,1	86,1	78,6	76,7	72,2	70	69,8	66,2	63,1	59,4	56,6	50,8	50,6	49,2	47,7	43,5	42	42,4	43,3	47,3	38,7	38,2
A66 – 2 Mazères-Saverdun	86,9	86,9	86,9	86,9	86,9	86,9	86,9	86,9	86,9	86,9	79,1	77,2	72,8	70,5	70,3	66,7	63,6	59,9	57,2	52,4	52,2	50,4	48,2	45,3	43,1	43,5	43,8	47,8	39,2	38,8
A66 – Péage de Pamiers	87,2	87,2	87,2	87,2	87,2	87,2	87,2	87,2	87,2	87,2	79,6	77,7	73,7	71,2	70,8	67,2	64,1	60,4	57,7	53,2	52,8	50,9	48,7	45,8	43,6	44	44,7	48,6	40,5	40,1
A66 – 3 Pamiers Nord	87,2	87,2	87,2	87,2	87,2	87,2	87,2	87,2	87,2	87,2	79,6	77,7	73,7	71,2	70,8	67,2	64,1	60,4	57,7	53,2	52,8	50,9	48,7	45,8	43,6	44	44,7	48,6	40,5	40,1
A66 – 4 Pamiers Sud	87,2	87,2	87,2	87,2	87,2	87,2	87,2	87,2	87,2	87,2	79,6	77,7	73,7	71,2	70,8	67,2	64,1	60,4	57,7	53,2	52,8	50,9	48,7	45,8	43,6	44	44,7	48,6	40,5	40,1
A61 – 19.1 Montgiscard	86,1	86,1	86,1	86,1	86,1	86,1	86,1	86,1	86,1	86,1	78,9	76,9	72,3	70,2	70	66,4	63,3	59,6	56,8	50,8	50,6	49,3	47,9	43,8	42	42,4	43,5	47,3	38,9	38,4
A61 – Péage de Toulouse sud/ouest	88,7	88,7	88,7	88,7	88,7	88,7	88,7	88,7	88,7	88,7	83,6	80,9	76,1	73,7	73,5	71,1	67,5	63,9	61,7	54,7	54,6	53,6	52,6	48,2	46,8	47,1	47,5	52,1	43,6	42,9
A61 – 19 Le Palays	88,7	88,7	88,7	88,7	88,7	88,7	88,7	88,7	88,7	88,7	83,6	80,9	76,1	73,7	73,5	71,1	67,5	63,9	61,7	54,7	54,6	53,6	52,6	48,2	46,8	47,1	47,5	52,1	43,6	42,9
A61 – Péage de Toulouse sud/est	89,6	89,6	89,6	89,6	89,6	89,6	89,6	89,6	89,6	89,6	84,5	81,8	77	74,6	74,4	72	68,4	64,8	62,6	55,6	55,5	54,5	53,5	49,1	47,7	48	48,4	53	44,5	43,8
A61 – 18 Montaudran	89,6	89,6	89,6	89,6	89,6	89,6	89,6	89,6	89,6	89,6	84,5	81,8	77	74,6	74,4	72	68,4	64,8	62,6	55,6	55,5	54,5	53,5	49,1	47,7	48	48,4	53	44,5	43,8
A61 – 17 Lasbordes	89,6	89,6	89,6	89,6	89,6	89,6	89,6	89,6	89,6	89,6	84,5	81,8	77	74,6	74,4	72	68,4	64,8	62,6	55,6	55,5	54,5	53,5	49,1	47,7	48	48,4	53	44,5	43,8
A61 – 16 Soupetard	89,6	89,6	89,6	89,6	89,6	89,6	89,6	89,6	89,6	89,6	84,5	81,8	77	74,6	74,4	72	68,4	64,8	62,6	55,6	55,5	54,5	53,5	49,1	47,7	48	48,4	53	44,5	43,8
A61 – 15 La Roseraie	89,6	89,6	89,6	89,6	89,6	89,6	89,6	89,6	89,6	89,6	84,5	81,8	77	74,6	74,4	72	68,4	64,8	62,6	55,6	55,5	54,5	53,5	49,1	47,7	48	48,4	53	44,5	43,8
A62 – 14 La Croix Daurade	89,6	89,6	89,6	89,6	89,6	89,6	89,6	89,6	89,6	89,6	84,5	81,8	77	74,6	74,4	72	68,4	64,8	62,6	55,6	55,5	54,5	53,5	49,1	47,7	48	48,4	53	44,5	43,8
A62 – 13 Borderouge	89,6	89,6	89,6	89,6	89,6	89,6	89,6	89,6	89,6	89,6	84,5	81,8	77	74,6	74,4	72	68,4	64,8	62,6	55,6	55,5	54,5	53,5	49,1	47,7	48	48,4	53	44,5	43,8
A62 – 12 Les Izards	89,6	89,6	89,6	89,6	89,6	89,6	89,6	89,6	89,6	89,6	84,5	81,8	77	74,6	74,4	72	68,4	64,8	62,6	55,6	55,5	54,5	53,5	49,1	47,7	48	48,4	53	44,5	43,8
A620 – 33 Sesquières	89,6	89,6	89,6	89,6	89,6	89,6	89,6	89,6	89,6	89,6	84,5	81,8	77	74,6	74,4	72	68,4	64,8	62,6	55,6	55,5	54,5	53,5	49,1	47,7	48	48,4	53	44,5	43,8

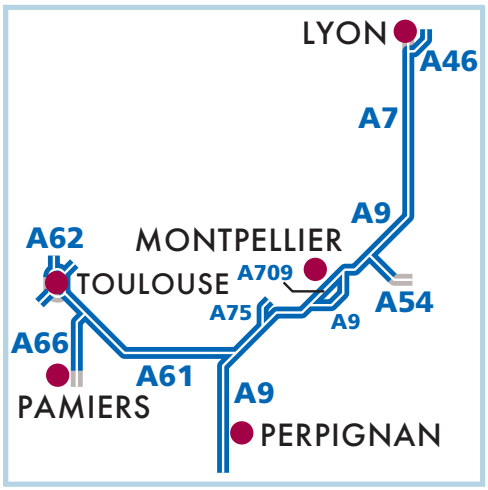

CLASSE 2

Tarifs applicables au 1er février 2025

A9 A61 A62 A66 A75 A709

	Lyon Marseille	(28) Vendargues	(29) Montpellier est	(30) Montpellier sud	(31) Montpellier ouest	(32) St-Jean-de-Védas	Péage de Montpellier St-Jean	(33) Sète	(34) Agde Pézenas	Péage de Béziers-Cabrials	(36) Béziers ouest	(37) Narbonne est	(38) Narbonne sud	(39) Sigean	(40) Leucate	(41) Perpignan nord	(42) Perpignan sud	(43) Le Boulou (péage en système fermé)	Péage du Perthus	(43) Le Boulou (péage en système ouvert)	Frontière Espagnole	(25) Lézignan	(24) Carcassonne est	(23) Carcassonne ouest	(22) Bram	(21) Castelnaudary	(20) Villefranche-de-Lauragais	(1) Nailloux	(2) Mazères-Saverdun	Péage de Pamiers	(3) Pamiers nord	(4) Pamiers sud	(19) Montgiscard	Péage de Toulouse sud/ouest	(19) Le Palays	Péage de Toulouse sud/est	(18) Montaudran	(17) Lasbordes	(16) Soupetard	(15) La Roseraie	(14) La Croix Daurade	(13) Borderouge	(12) Les Izards	(33) Sesquières	Espagne
(28) Vendargues	0																																												
(29) Montpellier est	0	0																																											
(30) Montpellier sud	0	0	0																																										
(31) Montpellier ouest	0	0	0	0																																									
(32) St-Jean-de-Védas	.	.	.	.	.																																								
Péage de Montpellier St-Jean	2,9	2,9	2,9	2,9	2,9	2,9																																							
(33) Sète	6	6	6	6	6	6	3,3																																						
(34) Agde Pézenas	7,5	7,5	7,5	7,5	7,5	7,5	5,6	1,5																																					
Péage de Béziers-Cabrials	9,7	9,7	9,7	9,7	9,7	9,7	6	2,6	1																																				
(36) Béziers ouest	14,7	14,7	14,7	14,7	14,7	14,7	10,2	5,6	4,4	3,2																																			
(37) Narbonne est	14,9	14,9	14,9	14,9	14,9	14,9	10,4	5,8	4,6	3,5	0,6																																		
(38) Narbonne sud	19,3	19,3	19,3	19,3	19,3	19,3	15	10,3	7,6	6,4	3,2	2,5																																	
(39) Sigean	20,6	20,6	20,6	20,6	20,6	20,6	15,9	12,1	10,3	7,4	4,7	3,7	1,1																																
(40) Leucate	25,9	25,9	25,9	25,9	25,9	25,9	21,1	16,9	15,9	13,2	9,7	8,4	5,1	3,2																															
(41) Perpignan nord	26,1	26,1	26,1	26,1	26,1	26,1	21,4	17,1	16,2	13,5	10	8,9	5,8	4,6	1,6																														
(42) Perpignan sud	29,7	29,7	29,7	29,7	29,7	29,7	27	22,2	19,8	18,3	15,6	14	11	8,5	4,1	2,6																													
(43) Le Boulou (péage en système fermé)	34,3	34,3	34,3	34,3	34,3	34,3	29,3	25,2	24,5	21,4	18,3	17,3	13,7	11,5	5,5	4,8	.																												
Péage du Perthus	.	.	.	.	.	.	.	.	.	.	.	.	.	.	.	.	.	.																												
(43) Le Boulou (péage en système ouvert)	34,3	34,3	34,3	34,3	34,3	34,3	29,3	25,2	24,5	21,4	18,3	17,3	13,7	11,5	5,5	4,8	.	.	1,5																										
Frontière Espagnole	19,2	19,2	19,2	19,2	19,2	19,2	14,9	9,9	7,2	6,3	4	2,7	4,9	5,8	12,1	12,5	15,9	18,8	.	18,8																									
(25) Lézignan	25	25	25	25	25	25	21,3	16,4	13,5	12,4	9,5	8,1	11,8	12,1	18	18,4	22,3	25,8	.	25,8	3,9																								
(24) Carcassonne est	25,4	25,4	25,4	25,4	25,4	25,4	21,8	16,9	14	12,9	10,4	8,6	12,3	12,6	18,5	18,9	22,7	26,2	.	26,2	5	1,1																						
(23) Carcassonne ouest	30,3	30,3	30,3	30,3	30,3	30,3	26,5	21,6	18	17,7	15,8	14,5	16,4	17	22	22,4	26,8	30,3	.	30,3	8,7	3,9	2,9																					
(22) Bram	32,8	32,8	32,8	32,8	32,8	32,8	26,9	23,7	20,5	19,8	17,5	16,3	18,2	19,3	24,8	25,2	27,7	32,6	.	32,6	11,1	5,9	4,8	2																				
(21) Castelnaudary	36,1	36,1	36,1	36,1	36,1	36,1	32,2	26,8	23,4	23,5	21,6	19,8	22,6	23	27,7	28,1	31,8	35,8	.	35,8	15,3	10,2	8,3	5,2	3,5																			
(20) Villefranche-de-Lauragais	36,5	36,5	36,5	36,5	36,5	36,5	32,7	27,6	24,5	24,1	22	21,2	23	23,6	28,1	28,5	32	36,2	.	36,2	16	11,3	10,2	6,8	5,2	1,3																		
(1) Nailloux	37	37	37	37	37	37	33,2	29,1	26,4	25,3	22,8	21,8	23,5	24,2	28,8	29,2	32,5	36,8	.	36,8	17,7	14,1	12,6	9,3	8,3	4,7	3,1																		
(2) Mazères-Saverdun	38	38	38	38	38	38	33,7	29,6	26,9	26,1	24,1	22,3	24,9	25,1	30	31	33	37,2	.	37,2	19,2	16	14,2	11	10	7,3	5,6	1,8																	
Péage de Pamiers	38	38	38	38	38	38	33,7	29,6	26,9	26,1	24,1	22,3	24,9	25,1	30	31	33	37,2	.	37,2	19,2	16	14,2	11	10	7,3	5,6	1,8	.																
(3) Pamiers nord	38	38	38	38	38	38	33,7	29,6	26,9	26,1	24,1	22,3	24,9	25,1	30	31	33	37,2	.	37,2	19,2	16	14,2	11	10	7,3	5,6	1,8	.	.															
(4) Pamiers sud	36,4	36,4	36,4	36,4	36,4	36,4	32,7	27,5	24,4	24	22	20,6	23	23,8	28,3	28,7	32	36,1	.	36,1	16,1	11	10,5	7,1	5,3	1,5	1,8	5	7,7	7,7	7,7														
(19) Montgiscard	41,2	41,2	41,2	41,2	41,2	41,2	37,1	32,3	29,5	28,1	26,4	24,6	26,4	27,8	32,8	33,1	36,6	41	.	41	20,3	15,3	14,3	9,9	7,3	3,7	4	7	9,6	9,6	9,6	2,1													
Péage de Toulouse sud/ouest	41,2	41,2	41,2	41,2	41,2	41,2	37,1	32,3	29,5	28,1	26,4	24,6	26,4	27,8	32,8	33,1	36,6	41	.	41	20,3	15,3	14,3	9,9	7,3	3,7	4	7	9,6	9,6	9,6	2,1	.											
(19) Le Palays	42,1	42,1	42,1	42,1	42,1	42,1	38	33,2	30,4	29	27,3	25,5	27,3	28,7	33,7	34	37,5	41,9	.	41,9	21,2	16,2	15,2	10,8	8,2	4,3	4,6	7,9	10,5	10,5	10,5	2,7	.	.										
Péage de Toulouse sud/est	42,1	42,1	42,1	42,1	42,1	42,1	38	33,2	30,4	29	27,3	25,5	27,3	28,7	33,7	34	37,5	41,9	.	41,9	21,2	16,2	15,2	10,8	8,2	4,3	4,6	7,9	10,5	10,5	10,5	2,7	.	0	.									
(18) Montaudran	42,1	42,1	42,1	42,1	42,1	42,1	38	33,2	30,4	29	27,3	25,5	27,3	28,7	33,7	34	37,5	41,9	.	41,9	21,2	16,2	15,2	10,8	8,2	4,3	4,6	7,9	10,5	10,5	10,5	2,7	.	0	.	0								
(17) Lasbordes	42,1	42,1	42,1	42,1	42,1	42,1	38	33,2	30,4	29	27,3	25,5	27,3	28,7	33,7	34	37,5	41,9	.	41,9	21,2	16,2	15,2	10,8	8,2	4,3	4,6	7,9	10,5	10,5	10,5	2,7	.	0	.	0	0							
(16) Soupetard	42,1	42,1	42,1	42,1	42,1	42,1	38	33,2	30,4	29	27,3	25,5	27,3	28,7	33,7	34	37,5	41,9	.	41,9	21,2	16,2	15,2	10,8	8,2	4,3	4,6	7,9	10,5	10,5	10,5	2,7	.	0	.	0	0	0						
(15) La Roseraie	42,1	42,1	42,1	42,1	42,1	42,1	38	33,2	30,4	29	27,3	25,5	27,3	28,7	33,7	34	37,5	41,9	.	41,9	21,2	16,2	15,2	10,8	8,2	4,3	4,6	7,9	10,5	10,5	10,5	2,7	.	0	.	0	0	0	0					
(14) La Croix Daurade	42,1	42,1	42,1	42,1	42,1	42,1	38	33,2	30,4	29	27,3	25,5	27,3	28,7	33,7	34	37,5	41,9	.	41,9	21,2	16,2	15,2	10,8	8,2	4,3	4,6	7,9	10,5	10,5	10,5	2,7	.	0	.	0	0	0	0	0				
(13) Borderouge	42,1	42,1	42,1	42,1	42,1	42,1	38	33,2	30,4	29	27,3	25,5	27,3	28,7	33,7	34	37,5	41,9	.	41,9	21,2	16,2	15,2	10,8	8,2	4,3	4,6	7,9	10,5	10,5	10,5	2,7	.	0	.	0	0	0	0	0	0			
(12) Les Izards	42,1	42,1	42,1	42,1	42,1	42,1	38	33,2	30,4	29	27,3	25,5	27,3	28,7	33,7	34	37,5	41,9	.	41,9	21,2	16,2	15,2	10,8	8,2	4,3	4,6	7,9	10,5	10,5	10,5	2,7		0	.	0	0	0	0	0	0			

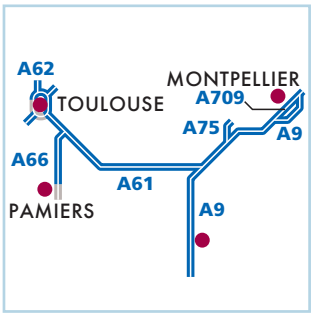

RN20 Tunnel du Puymorens

	Liaison	prix
N20	Pyrénées-Orientales / Ariège	16

A68 A61 A62

	Albi	(4) Gemil	(3) Montastruc	(2) Gragnague	Bretelle de Verfeil	Péage de Toulouse est	(1) L'Union	(14) La Croix Daurade	(13) Borderouge	(12) Les Izards	(33) Sesquières	(15) La Roseraie	(16) Soupetard	(17) Lasbordes	(18) Montaudran	(19) Le Palays	Toulouse
(4) Gemil	0																
(3) Montastruc	.	.															
(2) Gragnague	.	.	.														
Bretelle de Verfeil	2,7	2,7	2,7	2,7													
Péage de Toulouse est	2,7	2,7	2,7	2,7	2,7												
(1) L'Union	2,7	2,7	2,7	2,7	2,7	0,7											
(14) La Croix Daurade	2,7	2,7	2,7	2,7	2,7	0,7	0										
(13) Borderouge	2,7	2,7	2,7	2,7	2,7	0,7	0	0									
(12) Les Izards	2,7	2,7	2,7	2,7	2,7	0,7	0	0	0								
(33) Sesquières	2,7	2,7	2,7	2,7	2,7	0,7	0	0	0	0							
(15) La Roseraie	2,7	2,7	2,7	2,7	2,7	0,7	0	0	0	0	0						
(16) Soupetard	2,7	2,7	2,7	2,7	2,7	0,7	0	0	0	0	0	0					
(17) Lasbordes	2,7	2,7	2,7	2,7	2,7	0,7	0	0	0	0	0	0	0				
(18) Montaudran	2,7	2,7	2,7	2,7	2,7	0,7	0	0	0	0	0	0	0	0			
(19) Le Palays	2,7	2,7	2,7	2,7	2,7	0,7	0	0	0	0	0	0	0	0	0		

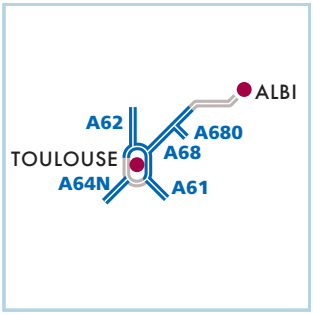

CLASSE 2

Tarifs applicables au 1er février 2025

A61 **A62** **A20** **A64** **A65**

Toulouse

	(19) Le Palays	(18) Montaudran	(17) Lasbordes	(16) Soupetard	(15) La Roseraie	(14) La Croix Daurade	(13) Borderouge	(12) Les Izards	Péage de Toulouse nord/est	(33) Sesquières	Péage de Toulouse nord/ouest	(11) Saint-Jory	(10.1) Eurocentre	(60) Montauban nord	(61) ZI nord	(62) Chaumes	(63) Beausoleil	(64) Sapiac	(65) La Molle	(66) Parages	(67) Moulis	(10) Montauban	(9) Castelsarrasin	(8) Valence-d'Agen	(7) Agen	(6.1) Agen Ouest	(6) Aiguillon	(5) Marmande	(4) La Réole	(3) Langon	(2) Podensac	Péage de Saint-Selve	(1.1) La Brède	(1) Bazas	(2) Captieux	(3) Roquefort	(4) Le Caloy	(6) Aire-sur-Adour nord	(7) Aire-sur-Adour sud	(8) Garlin	(9) Thèze	(1) Mousserolles	(1.1) Mouguerre Bourg	(2) Mouguerre Elizaberry	(3) Briscous	(4) Urt	(5) Guiche	Péage de Sames	(6) Peyrehorade	(7) Salies	(8) Orthez	(9) Artix	(9.1) Lescar	(10) Pau centre	(11) Soumoulou	(12) Tarbes ouest	(13) Tarbes est	(14) Tournay	(15) Capvern	(16) Lannemezan	(17) Montréjeau	(18) Saint-Gaudens	Péage de Lestelle	(19) Lestelle-de-Saint-Martory	(20) Saint-Martory	(21) Boussens
(18) Montaudran	0
(17) Lasbordes	0	0
(16) Soupetard	0	0	0
(15) La Roseraie	0	0	0	0
(14) La Croix Daurade	0	0	0	0	0
(13) Borderouge	0	0	0	0	0	0
(12) Les Izards	0	0	0	0	0	0	.
Péage de Toulouse nord/est	.	.	.	.	.	.	.	.
(33) Sesquières	0	0	0	0	0	0	.	.	.
Péage de Toulouse nord/ouest	.	.	.	.	.	.	.	.	.	.
(11) Saint-Jory	2	2	2	2	2	2	2	.	2	1,4	1,4
(10.1) Eurocentre	3,1	3,1	3,1	3,1	3,1	3,1	3,1	.	3,1	2,4	2,4	0,9
(60) Montauban nord	6,4	6,4	6,4	6,4	6,4	6,4	6,4	.	6,4	5,5	5,5	4,5	2,7
(61) ZI nord	6,4	6,4	6,4	6,4	6,4	6,4	6,4	.	6,4	5,5	5,5	4,5	2,7	0
(62) Chaumes	6,4	6,4	6,4	6,4	6,4	6,4	6,4	.	6,4	5,5	5,5	4,5	2,7	0	0
(63) Beausoleil	6,4	6,4	6,4	6,4	6,4	6,4	6,4	.	6,4	5,5	5,5	4,5	2,7	0	0	0
(64) Sapiac	6,4	6,4	6,4	6,4	6,4	6,4	6,4	.	6,4	5,5	5,5	4,5	2,7	0	0	0	0
(65) La Molle	6,4	6,4	6,4	6,4	6,4	6,4	6,4	.	6,4	5,5	5,5	4,5	2,7	0	0	0	0	0
(66) Parages	6,4	6,4	6,4	6,4	6,4	6,4	6,4	.	6,4	5,5	5,5	4,5	2,7	0	0	0	0	0	0
(67) Moulis	6,4	6,4	6,4	6,4	6,4	6,4	6,4	.	6,4	5,5	5,5	4,5	2,7	0	0	0	0	0	0	0
(10) Montauban	6,4	6,4	6,4	6,4	6,4	6,4	6,4	.	6,4	5,5	5,5	4,5	2,7	.	.	.	.	.	.	.	.
(9) Castelsarrasin	10,4	10,4	10,4	10,4	10,4	10,4	10,4	.	10,4	9,4	9,4	7	6,2	3,5	3,5	3,5	3,5	3,5	3,5	3,5	3,5	3,5
(8) Valence-d'Agen	13,7	13,7	13,7	13,7	13,7	13,7	13,7	.	13,7	12,7	12,7	10,9	9	6,9	6,9	6,9	6,9	6,9	6,9	6,9	6,9	6,9	2,8
(7) Agen	17,8	17,8	17,8	17,8	17,8	17,8	17,8	.	17,8	16,8	16,8	15,4	14,2	11,8	11,8	11,8	11,8	11,8	11,8	11,8	11,8	11,8	7,1	3,6
(6.1) Agen Ouest	20,7	20,7	20,7	20,7	20,7	20,7	20,7	.	20,7	19,7	19,7	18,2	16,7	14	14	14	14	14	14	14	14	14	8,6	4,9	0,8
(6) Aiguillon	20,8	20,8	20,8	20,8	20,8	20,8	20,8	.	20,8	19,8	19,8	18,4	16,9	14,2	14,2	14,2	14,2	14,2	14,2	14,2	14,2	14,2	10,7	7,5	4,1	3,9
(5) Marmande	26,6	26,6	26,6	26,6	26,6	26,6	26,6	.	26,6	25,6	25,6	23,8	21,3	20,8	20,8	20,8	20,8	20,8	20,8	20,8	20,8	20,8	16,4	12,4	8,2	8,1	3,6
(4) La Réole	28,9	28,9	28,9	28,9	28,9	28,9	28,9	.	28,9	27,9	27,9	24,2	23,5	22,3	22,3	22,3	22,3	22,3	22,3	22,3	22,3	22,3	18,6	15,6	10,5	10,4	5,9	2,6
(3) Langon	31	31	31	31	31	31	31	.	31	30	30	28,4	26,9	24,6	24,6	24,6	24,6	24,6	24,6	24,6	24,6	24,6	21,9	18,2	13,2	13	8,4	5,1	2,8
(2) Podensac	33,1	33,1	33,1	33,1	33,1	33,1	33,1	.	33,1	32,1	32,1	30,8	29,1	26,1	26,1	26,1	26,1	26,1	26,1	26,1	26,1	26,1	23	20,2	14,5	14,2	9,7	7,2	4,6	1,9
Péage de Saint-Selve	36	36	36	36	36	36	36	.	36	35	35	34,4	32,9	30,1	30,1	30,1	30,1	30,1	30,1	30,1	30,1	30,1	26,7	22,3	18,4	18,2	12,9	9,7	7,2	3,6	2,2
(1.1) La Brède	36	36	36	36	36	36	36	.	36	35	35	34,4	32,9	30,1	30,1	30,1	30,1	30,1	30,1	30,1	30,1	30,1	26,7	22,3	18,4	18,2	12,9	9,7	7,2	3,6	2,2	.
(1) Bazas	33,5	33,5	33,5	33,5	33,5	33,5	33,5	.	33,5	32,5	32,5	31,3	29	27,6	27,6	27,6	27,6	27,6	27,6	27,6	27,6	27,6	24,3	21,2	16,4	16,3	11,6	8,5	5,9	4,5	6,6	8,7	8,7
(2) Captieux	39,8	39,8	39,8	39,8	39,8	39,8	39,8	.	39,8	38,8	38,8	37,6	35,3	33,9	33,9	33,9	33,9	33,9	33,9	33,9	33,9	33,9	30,6	27,5	22,7	22,6	17,9	14,8	12,2	10,8	12,9	15	15	5
(3) Roquefort	49,6	49,6	49,6	49,6	49,6	49,6	49,6	.	49,6	48,6	48,6	47,4	45,1	43,7	43,7	43,7	43,7	43,7	43,7	43,7	43,7	43,7	40,4	37,3	32,5	32,4	27,7	24,6	22	20,6	22,7	24,8	24,8	12,9	7,9
(4) Le Caloy	53,3	53,3	53,3	53,3	53,3	53,3	53,3	.	53,3	52,3	52,3	51,1	48,8	47,4	47,4	47,4	47,4	47,4	47,4	47,4	47,4	47,4	44,1	41	36,2	36,1	31,4	28,3	25,7	24,3	26,4	28,5	28,5	17,1	10,9	3
(6) Aire-sur-Adour nord	62,6	62,6	62,6	62,6	62,6	62,6	62,6	.	62,6	61,6	61,6	60,4	58,1	56,7	56,7	56,7	56,7	56,7	56,7	56,7	56,7	56,7	53,4	50,3	45,5	45,4	40,7	37,6	35	33,6	35,7	37,8	37,8	23,3	18,3	10,4	7,4
(7) Aire-sur-Adour sud	62,6	62,6	62,6	62,6	62,6	62,6	62,6	.	62,6	61,6	61,6	60,4	58,1	56,7	56,7	56,7	56,7	56,7	56,7	56,7	56,7	56,7	53,4	50,3	45,5	45,4	40,7	37,6	35	33,6	35,7	37,8	37,8	24,9	19,9	12	9,1	0
(8) Garlin	62,7	62,7	62,7	62,7	62,7	62,7	62,7	.	62,7	61,7	61,7	60,5	58,2	56,8	56,8	56,8	56,8	56,8	56,8	56,8	56,8	56,8	53,5	50,4	45,6	45,5	40,8	37,7	35,1	33,7	35,8	37,9	37,9	27,7	22,7	14,9	11,9	4,5	.
(9) Thèze	72,6	72,6	72,6	72,6	72,6	72,6	72,6	.	72,6	71,6	71,6	70,4	68,1	66,7	66,7	66,7	66,7	66,7	66,7	66,7	66,7	66,7	63,4	60,3	55,5	55,4	50,7	47,6	45	43,6	45,7	47,8	47,8	31,2	26,2	18,4	15,4	10	.	3,6
(1) Mousserolles	92,9	92,9	92,9	92,9	92,9	92,9	92,9	.	92,9	91,9	91,9	90,7	88,4	87	87	87	87	87	87	87	87	87	83,7	80,6	75,8	75,7	71	67,9	65,3	63,9	66	68,1	68,1	50,2	45,2	43,3	39,5	30,2	.	24,7	20,2
(1.1) Mouguerre Bourg	92,9	92,9	92,9	92,9	92,9	92,9	92,9	.	92,9	91,9	91,9	90,7	88,4	87	87	87	87	87	87	87	87	87	83,7	80,6	75,8	75,7	71	67,9	65,3	63,9	66	68,1	68,1	50,2	45,2	43,3	39,5	30,2	.	24,7	20,2	0
(2) Mouguerre Elizaberry	92,9	92,9	92,9	92,9	92,9	92,9	92,9	.	92,9	91,9	91,9	90,7	88,4	87	87	87	87	87	87	87	87	87	83,7	80,6	75,8	75,7	71	67,9	65,3	63,9	66	68,1	68,1	50,2	45,2	43,3	39,5	30,2	.	24,7	20,2	0	0
(3) Briscous	92,9	92,9	92,9	92,9	92,9	92,9	92,9	.	92,9	91,9	91,9	90,7	88,4	87	87	87	87	87	87	87	87	87	83,7	80,6	75,8	75,7	71	67,9	65,3	63,9	66	68,1	68,1	50,2	45,2	43,3	39,5	30,2	.	24,7	20,2	0	0	0
(4) Urt	92,9	92,9	92,9	92,9	92,9	92,9	92,9	.	92,9	91,9	91,9	90,7	88,4	87	87	87	87	87	87	87	87	87	83,7	80,6	75,8	75,7	71	67,9	65,3	63,9	66	68,1	68,1	50,2	45,2	43,3	39,5	30,2	.	24,7	20,2	0	0	0	0
(5) Guiche	.	.	.	.	.	.	.	.	.	.	.	.	.	.	.	.	.	.	.	.	.	.	.	.	.	.	.	.	.	.	.	.	.	.	.	.	.	.	.	.	.	1,3	1,3	1,3	1,3	1,3
Péage de Sames	92,9	92,9	92,9	92,9	92,9	92,9	92,9	.	92,9	91,9	91,9	90,7	88,4	87	87	87	87	87	87	87	87	87	83,7	80,6	75,8	75,7	71	67,9	65,3	63,9	66	68,1	68,1	50,2	45,2	43,3	39,5	30,2	.	24,7	20,2	.	.	.	.	.	.
(6) Peyrehorade	89	89	89	89	89	89	89	.	89	88	88	86,8	84,5	83,1	83,1	83,1	83,1	83,1	83,1	83,1	83,1	83,1	79,8	76,7	71,9	71,8	67,1	64	61,4	60	62,1	64,2	64,2	46,3	41,3	39,4	35,6	26,3	.	20,8	16,3	3,9	3,9	3,9	3,9	3,9	.	3,9
(7) Salies	85,3	85,3	85,3	85,3	85,3	85,3	85,3	.	85,3	84,3	84,3	83,1	80,8	79,4	79,4	79,4	79,4	79,4	79,4	79,4	79,4	79,4	76,1	73	68,2	68,1	63,4	60,3	57,7	56,3	58,4	60,5	60,5	42,6	37,6	35,7	31,9	22,6	.	17,1	12,6	6,3	6,3	6,3	6,3	6,3	.	6,3	2,5
(8) Orthez	83,7	83,7	83,7	83,7	83,7	83,7	83,7	.	83,7	82,7	82,7	81,5	79,2	77,8	77,8	77,8	77,8	77,8	77,8	77,8	77,8	77,8	74,5	71,4	66,6	66,5	61,8	58,7	56,1	54,7	56,8	58,9	58,9	41	36	34,1	30,3	21	.	15,5	11	8,7	8,7	8,7	8,7	8,7	.	8,7	5,6	2,1
(9) Artix	81	81	81	81	81	81	81	.	81	80	80	78,8	76,5	75,1	75,1	75,1	75,1	75,1	75,1	75,1	75,1	75,1	71,8	68,7	63,9	63,8	59,1	56	53,4	52	54,1	56,2	56,2	38,3	33,3	31,4	27,6	18,3	.	12,8	8,3	12,2	12,2	12,2	12,2	12,2	.	12,2	8,5	4,6	3
(9.1) Lescar	79,8	79,8	79,8	79,8	79,8	79,8	79,8	.	79,8	78,8	78,8	77,6	75,3	73,9	73,9	73,9	73,9	73,9	73,9	73,9	73,9	73,9	70,6	67,5	62,7	62,6	57,9	54,8	52,2	50,8	52,9	55	55	37,1	32,1	30,2	26,4	17,1	.	11,6	7,1	14,7	14,7	14,7	14,7	14,7	.	14,7	10,7	6,8	5,2	1,9
(10) Pau centre	80,9	80,9	80,9	80,9	80,9	80,9	80,9	.	80,9	79,9	79,9	78,7	76,4	75	75	75	75	75	75	75	75	75	71,7	68,6	63,8	63,7	59	55,9	53,3	51,9	54	56,1	56,1	38,2	33,2	31,3	27,5	18,2	.	12,7	8,2	15,4	15,4	15,4	15,4	15,4	.	15,4	11,9	7,2	5,8	3	0,6
(11) Soumoulou	82,1	82,1	82,1	82,1	82,1	82,1	82,1	.	82,1	81,1	81,1	79,9	77,6	76,2	76,2	76,2	76,2	76,2	76,2	76,2	76,2	76,2	72,9	69,8	65	64,9	60,2	57,1	54,5	53,1	55,2	57,3	57,3	39,4	34,4	32,5	28,7	19,4	.	13,9	9,4	16,3	16,3	16,3	16,3	16,3	.	16,3	12,6	8,4	6,6	3,9	2,5	1,8
(12) Tarbes ouest	85,7	85,7	85,7	85,7	85,7	85,7	85,7	.	85,7	84,7	84,7	83,5	81,2	79,8	79,8	79,8	79,8	79,8	79,8	79,8	79,8	79,8	76,5	73,4	68,6	68,5	63,8	60,7	58,1	56,7	58,8	60,9	60,9	43	38	36,1	32,3	23	.	17,5	13	22,1	22,1	22,1	22,1	22,1	.	22,1	17,7	13,2	11,9	8	5,9	4,8	3,1
(13) Tarbes est	86,1	86,1	86,1	86,1	86,1	86,1	86,1	.	86,1	85,1	85,1	83,9	81,6	80,2	80,2	80,2	80,2	80,2	80,2	80,2	80,2	80,2	76,9	73,8	69	68,9	64,2	61,1	58,5	57,1	59,2	61,3	61,3	43,4	38,4	36,5	32,7	23,4	.	17,9	13,4	22,4	22,4	22,4	22,4	22,4	.	22,4	18	13,6	12,2	8,3	6,6	5,7	4,2	1
(14) Tournay	87,4	87,4	87,4	87,4	87,4	87,4	87,4	.	87,4	86,4	86,4	85,2	82,9	81,5	81,5	81,5	81,5	81,5	81,5	81,5	81,5	81,5	78,2	75,1	70,3	70,2	65,5	62,4	59,8	58,4	60,5	62,6	62,6	44,7	39,7	37,8	34	24,7	.	19,2	14,7	23	23	23	23	23	.	23	18,3	14,3	12,9	9,3	7,6	6,8	5,1	1,7	0
(15) Capvern	88,3	88,3	88,3	88,3	88,3	88,3	88,3	.	88,3	87,3	87,3	86,1	83,8	82,4	82,4	82,4	82,4	82,4	82,4	82,4	82,4	82,4	79,1	76	71,2	71,1	66,4	63,3	60,7	59,3	61,4	63,5	63,5	45,6	40,6	38,7	34,9	25,6	.	20,1	15,6	23,4	23,4	23,4	23,4	23,4	.	23,4	19	14,8	13,5	9,9	8,5	7,4	5,7	2,4	0	0
(16) Lannemezan	89,3	89,3	89,3	89,3	89,3	89,3	89,3	.	89,3	88,3	88,3	87,1	84,8	83,4	83,4	83,4	83,4	83,4	83,4	83,4	83,4	83,4	80,1	77	72,2	72,1	67,4	64,3	61,7	60,3	62,4	64,5	64,5	46,6	41,6	39,7	35,9	26,6	.	21,1	16,6	24,8	24,8	24,8	24,8	24,8	.	24,8	19,7	16,3	14,9	11,2	9,4	8,3	6,5	3,4	1,9	1,2	0,6
(17) Montréjeau	92,6	92,6	92,6	92,6	92,6	92,6	92,6	.	92,6	91,6	91,6	90,4	88,1	86,7	86,7	86,7	86,7	86,7	86,7	86,7	86,7	86,7	83,4	80,3	75,5	75,4	70,7	67,6	65	63,6	65,7	67,8	67,8	49,9	44,9	43	39,2	29,9	.	24,4	19,9	28	28	28	28	28	.	28	23,9	20,1	18,7	15,4	12,6	11,6	9,9	6,3	5,3	4,2	3,6	2,6
(18) Saint-Gaudens	93,7	93,7	93,7	93,7	93,7	93,7	93,7	.	93,7	92,7	92,7	91,5	89,2	87,8	87,8	87,8	87,8	87,8	87,8	87,8	87,8	87,8	84,5	81,4	76,6	76,5	71,8	68,7	66,1	64,7	66,8	68,9	68,9	51	46	44,1	40,3	31	.	25,5	21	29,5	29,5	29,5	29,5	29,5	.	29,5	24,9	21,4	20	16	14,2	13	11,3	7,5	6,4	5,5	4,8	4,4	2,2
Péage de Lestelle	99,1	99,1	99,1	99,1	99,1	99,1	99,1	.	99,1	98,1	98,1	96,9	94,6	93,2	93,2	93,2	93,2	93,2	93,2	93,2	93,2	93,2	89,9	86,8	82	81,9	77,2	74,1	71,5	70,1	72,2	74,3	74,3	56,4	51,4	49,5	45,7	36,4	.	30,9	26,4	35,7	35,7	35,7	35,7	35,7	.	35,7	31,5	26,6	25,1	21,1	19,3	18,3	16,6	12,6	11,4	10,1	9,6	9	7	3,8
(19) Lestelle-de-Saint-Martory	.	.	.	.	.	.	.	.	.	.	.	.	.	.	.	.	.	.	.	.	.	.	.	.	.	.	.	.	.	.	.	.	.	.	.	.	.	.	.	.	.	.	.	.	.	.	.	.	.	.	.	.	.	.	.	.	.	.	.	.	.	.	.
(20) Saint-Martory	99,1	99,1	99,1	99,1	99,1	99,1	99,1	.	99,1	98,1	98,1	96,9	94,6	93,2	93,2	93,2	93,2	93,2	93,2	93,2	93,2	93,2	89,9	86,8	82	81,9	77,2	74,1	71,5	70,1	72,2	74,3	74,3	56,4	51,4	49,5	45,7	36,4	.	30,9	26,4	35,7	35,7	35,7	35,7	35,7	.	35,7	31,5	26,6	25,1	21,1	19,3	18,3	16,6	12,6	11,4	10,1	9,6	9	7	3,8	.	2,4
(21) Boussens	99,1	99,1	99,1	99,1	99,1	99,1	99,1	.	99,1	98,1	98,1	96,9	94,6	93,2	93,2	93,2	93,2	93,2	93,2	93,2	93,2	93,2	89,9	86,8	82	81,9	77,2	74,1	71,5	70,1	72,2	74,3	74,3	56,4	51,4	49,5	45,7	36,4	.	30,9	26,4	35,7	35,7	35,7	35,7	35,7	.	35,7	31,5	26,6	25,1	21,1	19,3	18,3	16,6	12,6	11,4	10,1	9,6	9	7	3,8	.	2,4	0
(22) Martres-Tolosane	99,1	99,1	99,1	99,1	99,1	99,1	99,1	.	99,1	98,1	98,1	96,9	94,6	93,2	93,2	93,2	93,2	93,2	93,2	93,2	93,2	93,2	89,9	86,8	82	81,9	77,2	74,1	71,5	70,1	72,2	74,3	74,3	56,4	51,4	49,5	45,7	36,4	.	30,9	26,4	35,7	35,7	35,7	35,7	35,7	.	35,7	31,5	26,6	25,1	21,1	19,3	18,3	16,6	12,6	11,4	10,1	9,6	9	7	3,8	.	2,4	0	0

Toulouse

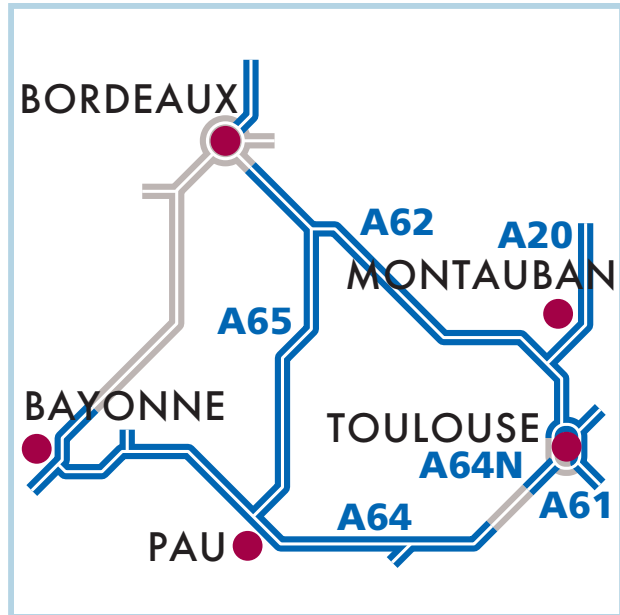

Le prix du péage peut inclure le prix du péage des trajets d'autres sociétés d'autoroutes au nom et pour le compte desquelles agit la société Autoroutes du Sud de la France percevant le péage en sortie.

A64 nord

Bayonne

	(35) Muret nord	Péage de Muret	(36) Roques	(37) Francazal
Péage de Muret	2,9			
(36) Roques	.	.		
(37) Francazal	2,9	2,9	0	
(38) Le Chapitre	2,9	2,9	0	0

Toulouse

CLASSE 2

Tarifs applicables au 1er février 2025

A63

Espagne → Bordeaux

	1 Biriatou	Péage de Biriatou	2 St-Jean-de-Luz sud	3 St-Jean-de-Luz nord	4 Biarritz (demi-échangeur sud)	Péage de la Négresse	5 Biarritz (demi-échangeur nord)	5 Bayonne sud	5.1 Bayonne Mousserolles	6 Bayonne nord	7 Ondres	8 Capbreton (demi-échangeur sud)	Péage de Bénesse-Marenne	8 Capbreton (demi-échangeur nord)
Péage de Biriatou	3													
2 St-Jean-de-Luz sud	3	3												
3 St-Jean-de-Luz nord	3	3	1,2											
4 Biarritz (demi-échangeur sud)	5	5	3,2	2										
Péage de la Négresse	7	7	5,2	4	.									
5 Biarritz (demi-échangeur nord)	.	.	.	.	.	.								
5 Bayonne sud	7	7	5,2	4	.	4	2							
5.1 Bayonne Mousserolles	7	7	5,2	4	.	4	2	1,3						
6 Bayonne nord	7	7	5,2	4	.	4	2	1,3	0					
7 Ondres	8,7	8,7	6,9	5,7	.	5,7	3,7	3	1,7	1,7				
8 Capbreton (demi-échangeur sud)	10,1	10,1	8,3	7,1	.	7,1	5,1	4,4	3,1	3,1	3,1			
Péage de Bénesse-Marenne	13,6	13,6	11,8	10,6	.	10,6	8,6	7,8	6,6	6,6	6,6	.		
8 Capbreton (demi-échangeur nord)	.	.	.	.	.	.	.	.	.	.	.	.	.	
9 St-Geours-de-Maremne	13,6	13,6	11,8	10,6	.	10,6	8,6	7,8	6,6	6,6	6,6	.	6,6	3,1

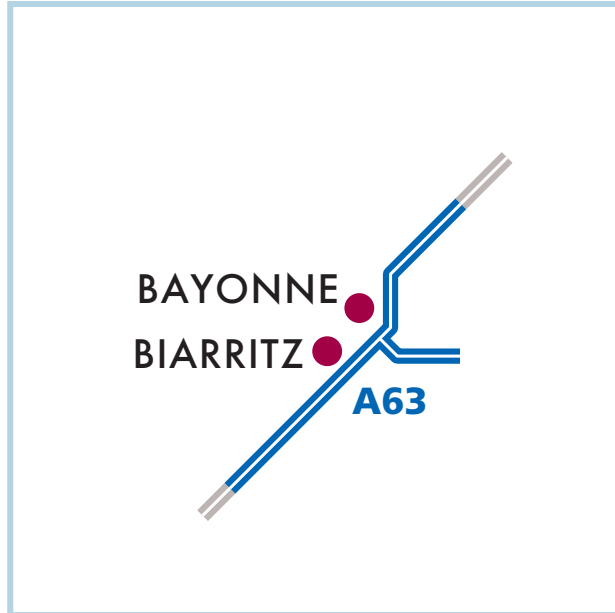

A20

Montauban → Brive

	67 Moulis	66 Parages	65 La Molle	64 Sapiac	63 Beausoleil	62 Chaumes	61 ZI nord	60 Montauban nord	Péage de Montauban nord	59 Caussade	58 Cahors sud	57 Cahors nord	56 Labastide Murat	55 Souillac	Péage de Gignac	54 Martel
66 Parages	0															
65 La Molle	0	0														
64 Sapiac	0	0	0													
63 Beausoleil	0	0	0	0												
62 Chaumes	0	0	0	0	0											
61 ZI nord	0	0	0	0	0	0										
60 Montauban nord	0	0	0	0	0	0	0									
Péage de Montauban nord	.	.	.	.	.	.	.	.								
59 Caussade	2,6	2,6	2,6	2,6	2,6	2,6	2,6	2,6	2,6							
58 Cahors sud	7,2	7,2	7,2	7,2	7,2	7,2	7,2	7,2	7,2	3,7						
57 Cahors nord	10,9	10,9	10,9	10,9	10,9	10,9	10,9	10,9	10,9	7,7	3,7					
56 Labastide Murat	16	16	16	16	16	16	16	16	16	11,3	7,5	3,7				
55 Souillac	21,2	21,2	21,2	21,2	21,2	21,2	21,2	21,2	21,2	15,8	11,8	8	3,9			
Péage de Gignac	24,6	24,6	24,6	24,6	24,6	24,6	24,6	24,6	24,6	19,9	16,3	12,1	9,6	3,6		
54 Martel	.	.	.	.	.	.	.	.	.	.	.	.	.	.	.	
53 Nespouls	24,6	24,6	24,6	24,6	24,6	24,6	24,6	24,6	24,6	19,9	16,3	12,1	9,6	3,6	.	1,2

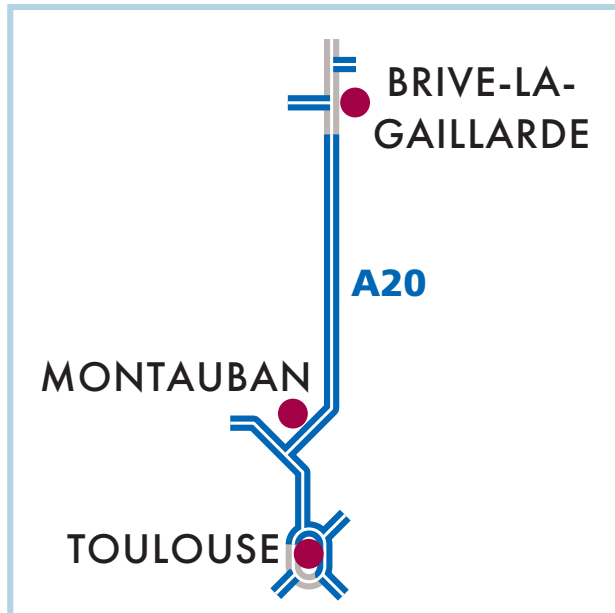

A89

Brive → Bordeaux

	A 20 limite de concession	19 Brive ouest	18 Mansac Terrasson	17 La Bachellerie	Péage de Thenon	17 Thenon est	16 Périgueux est	15 Périgueux sud	14 Périgueux ouest	Péage de Mussidan	13.1 Mussidan est	13 Mussidan sud	12 Montpon-Ménestérol	11 Coutras	10 Libourne nord	Péage d'Arveyres	9 Libourne ouest
19 Brive ouest	.																
18 Mansac Terrasson	1,6	1,6															
17 La Bachellerie	5,2	5,2	5,2														
Péage de Thenon	13,1	13,1	13,1	.													
17 Thenon est	.	.	.	.	.												
16 Périgueux est	13,1	13,1	13,1	.	13,1	7											
15 Périgueux sud	13,1	13,1	13,1	.	13,1	7	0										
14 Périgueux ouest	13,1	13,1	13,1	.	13,1	7	0	0									
Péage de Mussidan	.	.	.	.	.	.	.	.	.								
13.1 Mussidan est	.	.	.	.	.	.	.	.	.	.							
13 Mussidan sud	18,6	18,6	18,6	.	18,6	12,5	5,5	5,5	5,5	5,5	1,5						
12 Montpon-Ménestérol	22	22	22	.	22	15,9	8,9	8,9	8,9	8,9	5,3	2,7					
11 Coutras	26	26	26	.	26	19,9	12,9	12,9	12,9	12,9	9,4	6,8	3,3				
10 Libourne nord	28,1	28,1	28,1	.	28,1	22	15	15	15	15	12,4	9,4	5,8	2,1			
Péage d'Arveyres	30,3	30,3	30,3	.	30,3	24,2	17,2	17,2	17,2	17,2	15,6	12,7	8,1	4,3	1,7		
9 Libourne ouest	.	.	.	.	.	.	.	.	.	.	.	.	.	.	.	.	
Bordeaux limite de concession	30,3	30,3	30,3	.	30,3	24,2	17,2	17,2	17,2	17,2	15,6	12,7	8,1	4,3	1,7	.	0

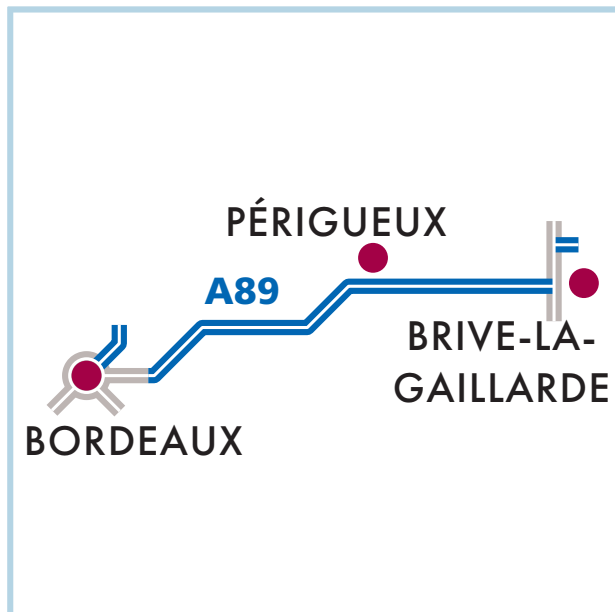

CLASSE 2

Tarifs applicables au 1er février 2025

A10 A83 A837 A87

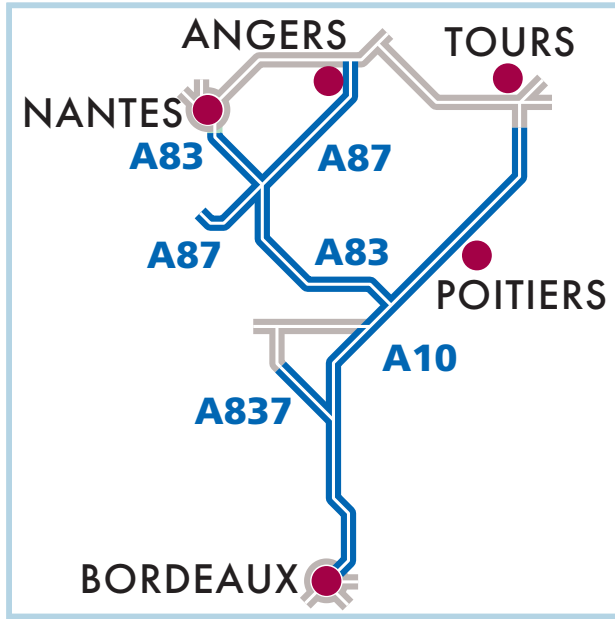

Le prix du péage peut inclure le prix du péage des trajets d'autres sociétés d'autoroutes au nom et pour le compte desquelles agit la société Autoroutes du Sud de la France percevant le péage en sortie.

Paris

	Péage de Tours centre	(25) Sainte-Maure	(26) Châtellerault nord	(27) Châtellerault sud	(28) Futuroscope	(29) Poitiers nord	(30) Poitiers sud	(31) St-Maixent-Soudan	(11) Niort est	(10) Niort nord	(9) Niort ouest	(8) Fontenay centre	(7.1) Fontenay ouest	(7) Sainte-Hermine	(6) Chantonnay	(5) Les Essarts	(33) La Roche-sur-Yon ouest	(32) La Roche-sur-Yon sud	(31) La Roche-sur-Yon centre	(30) La Roche-sur-Yon est	Péage de La Roche-sur-Yon	(29) Les Herbiers	(28) La Verrie	(27) Cholet sud	(26) Cholet nord	(25) Chemillé	Péage de Beaulieu-s.-Layon	(24) Thouarcé	(23) Mûrs-Érigné	(22.1) Grand-Clos	(22) Haute-Perche	(21) Sorges	(20) La Monnaie	(19) La Foucaudière	(18.2) Bd d'Estienne d'Orves	(18.1) Hanipet	(17) RD 347	(16) La Bouvinerie	(15) RD 323	(14) Gatignolle	(4) Montaigu	(3) Aigrefeuille	Péage du Bignon	(2) La Cour-Neuve	(32) Vouillé	(33) La Rochelle Niort sud	(34) St-Jean-d'Angély	(31) Rochefort ouest	(32) Rochefort nord	(33) Tonnay-Charente	(34) Tonnay-Charente	Péage de Cabariot	(35) Saintes	(36) Pons	(37) Mirambeau	(38) St-Aubin-de-Blaye	Péage de Virsac	(39) Libourne/St-Antoine	(40a) Blaye	(40b) St-André-de-Cubzac	(41) Ambes	(42) Ambarès/St-Loubès	(43) Sainte-Eulalie	(44) Carbon-Blanc
(25) Sainte-Maure	6,8
(26) Châtellerault nord	12,4	4,3
(27) Châtellerault sud	14,7	4,8	1,5
(28) Futuroscope	17,6	7,8	3,9	2,2
(29) Poitiers nord	19,9	9,7	5,2	3,9	1,2
(30) Poitiers sud	21,5	13	7,6	6	3	2,2
(31) St-Maixent-Soudan	26,2	17,7	12,3	10,7	7,7	6,9	4,7
(11) Niort est	30,4	21,9	16,5	14,9	11,9	11,1	8,9	2,8
(10) Niort nord	31,8	23,3	17,9	16,3	13,3	12,5	10,3	4,6	1,1
(9) Niort ouest	33,9	25,4	20	18,4	15,4	14,6	12,4	8,1	3,8	2,6
(8) Fontenay centre	38	29,5	24,1	22,5	19,5	18,7	16,5	10,8	6,2	5	1,6
(7.1) Fontenay ouest	38,1	29,6	24,2	22,6	19,6	18,8	16,6	11,2	6,5	5,5	2,2	0,6
(7) Sainte-Hermine	40,2	31,7	26,3	24,7	21,7	20,9	18,7	13,4	10,3	7,9	5,5	3	2,4
(6) Chantonnay	44,1	35,6	30,2	28,6	25,6	24,8	22,6	16,2	13	11,5	8	4,8	4,7	2,1
(5) Les Essarts	45,2	36,7	31,3	29,7	26,7	25,9	23,7	18,7	13,7	12,5	10,9	7,7	7,4	5,5	2,6
(33) La Roche-sur-Yon ouest	45,7	37,2	31,8	30,2	27,2	26,4	24,2	20,1	16,7	15,7	13,1	11	10,7	8,7	6,7	5,1
(32) La Roche-sur-Yon sud	45,7	37,2	31,8	30,2	27,2	26,4	24,2	20,1	16,7	15,7	13,1	11	10,7	8,7	6,7	5,1	0
(31) La Roche-sur-Yon centre	45,7	37,2	31,8	30,2	27,2	26,4	24,2	20,1	16,7	15,7	13,1	11	10,7	8,7	6,7	5,1	0	0
(30) La Roche-sur-Yon est	45,7	37,2	31,8	30,2	27,2	26,4	24,2	20,1	16,7	15,7	13,1	11	10,7	8,7	6,7	5,1	0	0	0
Péage de La Roche-sur-Yon	45,7	37,2	31,8	30,2	27,2	26,4	24,2	20,1	16,7	15,7	13,1	11	10,7	8,7	6,7	5,1	.	.	.	.
(29) Les Herbiers	47,9	39,4	34	32,4	29,4	28,6	26,4	21,1	18,1	16,4	13,1	11,4	10,3	8,6	5,4	2,3	7,6	7,6	7,6	7,6	7,6
(28) La Verrie	48,1	39,6	34,2	32,6	29,6	28,8	26,6	22,8	18,6	17,3	15,5	13,5	12,7	10,8	7,3	4,1	9,6	9,6	9,6	9,6	9,6	0,9
(27) Cholet sud	48,3	39,8	34,4	32,8	29,8	29	26,8	23	18,8	17,4	15,7	13,7	12,8	10,9	7,8	4,9	9,8	9,8	9,8	9,8	9,8	2,6	1,5
(26) Cholet nord	48,5	40	34,6	33	30	29,2	27	23,5	20,3	18,3	17,2	15,3	14,7	13,9	10,6	7,8	12,8	12,8	12,8	12,8	12,8	4,4	2,9	1,2
(25) Chemillé	50,4	41,9	36,5	34,9	31,9	31,1	28,9	26,5	22,4	20,8	19,8	18,8	18,4	17,2	13,2	9,9	15,6	15,6	15,6	15,6	15,6	7,6	5,2	4,6	2,6
Péage de Beaulieu-s.-Layon	53,7	45,2	39,8	38,2	35,2	34,4	32,2	29,3	26,1	24,9	23,9	22,6	22,4	22,3	18,1	14,8	20,2	20,2	20,2	20,2	20,2	12,1	10	9,6	7,1	4,1
(24) Thouarcé	53,7	45,2	39,8	38,2	35,2	34,4	32,2	29,3	26,1	24,9	23,9	22,6	22,4	22,3	18,1	14,8	20,2	20,2	20,2	20,2	20,2	12,1	10	9,6	7,1	4,1	.
(23) Mûrs-Érigné	53,7	45,2	39,8	38,2	35,2	34,4	32,2	29,3	26,1	24,9	23,9	22,6	22,4	22,3	18,1	14,8	20,2	20,2	20,2	20,2	20,2	12,1	10	9,6	7,1	4,1	.	1,2
(22.1) Grand-Clos	.	.	.	.	.	.	.	.	.	.	.	.	.	.	.	.	.	.	.	.	.	.	.	.	.	.	.	.	.
(22) Haute-Perche	53,7	45,2	39,8	38,2	35,2	34,4	32,2	29,3	26,1	24,9	23,9	22,6	22,4	22,3	18,1	14,8	20,2	20,2	20,2	20,2	20,2	12,1	10	9,6	7,1	4,1	.	1,2	0	0
(21) Sorges	53,7	45,2	39,8	38,2	35,2	34,4	32,2	29,3	26,1	24,9	23,9	22,6	22,4	22,3	18,1	14,8	20,2	20,2	20,2	20,2	20,2	12,1	10	9,6	7,1	4,1	.	1,2	0	0	0
(20) La Monnaie	53,7	45,2	39,8	38,2	35,2	34,4	32,2	29,3	26,1	24,9	23,9	22,6	22,4	22,3	18,1	14,8	20,2	20,2	20,2	20,2	20,2	12,1	10	9,6	7,1	4,1	.	1,2	0	0	0	0
(19) La Foucaudière	53,7	45,2	39,8	38,2	35,2	34,4	32,2	29,3	26,1	24,9	23,9	22,6	22,4	22,3	18,1	14,8	20,2	20,2	20,2	20,2	20,2	12,1	10	9,6	7,1	4,1	.	1,2	0	0	0	0	0
(18.2) Bd d'Estienne d'Orves	.	.	.	.	.	.	.	.	.	.	.	.	.	.	.	.	.	.	.	.	.	.	.	.	.	.	.	.	.	.	0	0	0	0
(18.1) Hanipet	53,7	45,2	39,8	38,2	35,2	34,4	32,2	29,3	26,1	24,9	23,9	22,6	22,4	22,3	18,1	14,8	20,2	20,2	20,2	20,2	20,2	12,1	10	9,6	7,1	4,1	.	1,2	0	0	0	0	0	0	0
(17) RD 347	53,7	45,2	39,8	38,2	35,2	34,4	32,2	29,3	26,1	24,9	23,9	22,6	22,4	22,3	18,1	14,8	20,2	20,2	20,2	20,2	20,2	12,1	10	9,6	7,1	4,1	.	1,2	0	0	0	0	0	0	0	0
(16) La Bouvinerie	53,7	45,2	39,8	38,2	35,2	34,4	32,2	29,3	26,1	24,9	23,9	22,6	22,4	22,3	18,1	14,8	20,2	20,2	20,2	20,2	20,2	12,1	10	9,6	7,1	4,1	.	1,2	0	0	0	0	0	0	0	0	0
(15) RD 323	53,7	45,2	39,8	38,2	35,2	34,4	32,2	29,3	26,1	24,9	23,9	22,6	22,4	22,3	18,1	14,8	20,2	20,2	20,2	20,2	20,2	12,1	10	9,6	7,1	4,1	.	1,2	0	0	0	0	0	0	0	0	0	0
(14) Gatignolle	53,7	45,2	39,8	38,2	35,2	34,4	32,2	29,3	26,1	24,9	23,9	22,6	22,4	22,3	18,1	14,8	20,2	20,2	20,2	20,2	20,2	12,1	10	9,6	7,1	4,1	.	1,2	0	0	0	0	0	0	0	0	0	0	0
(4) Montaigu	47,8	39,3	33,9	32,3	29,3	28,5	26,3	22	19,2	17,5	15	11,6	11,1	9,5	6,5	3,5	7,6	7,6	7,6	7,6	7,6	5,5	6,9	7,7	10,3	12,9	17,2	17,2	17,2	.	17,2	17,2	17,2	17,2	.	17,2	17,2	17,2	17,2	17,2
(3) Aigrefeuille	48	39,5	34,1	32,5	29,5	28,7	26,5	25	22,3	20,3	17,9	14,3	13,5	12,2	9	5,7	10,8	10,8	10,8	10,8	10,8	8,3	9,3	10	11,7	14,3	18,4	18,4	18,4	.	18,4	18,4	18,4	18,4	.	18,4	18,4	18,4	18,4	18,4	2
Péage du Bignon	48,2	39,7	34,3	32,7	29,7	28,9	26,7	25,4	23,2	21,2	18,7	15,5	15,3	15,1	10,8	7,5	11,8	11,8	11,8	11,8	11,8	9,2	10,8	11	11,8	14,5	18,5	18,5	18,5	.	18,5	18,5	18,5	18,5	.	18,5	18,5	18,5	18,5	18,5	3,4	1,4
(2) La Cour-Neuve	48,2	39,7	34,3	32,7	29,7	28,9	26,7	25,4	23,2	21,2	18,7	15,5	15,3	15,1	10,8	7,5	11,8	11,8	11,8	11,8	11,8	9,2	10,8	11	11,8	14,5	18,5	18,5	18,5	.	18,5	18,5	18,5	18,5	.	18,5	18,5	18,5	18,5	18,5	3,4	1,4	.
(32) Vouillé	30,9	22,4	17	15,4	12,4	11,6	9,4	3,1	1	2,7	4,9	7,8	8,3	11,3	13,3	16,4	17,9	17,9	17,9	17,9	17,9	19,3	20,3	20,4	20,8	23,6	27,6	27,6	27,6	.	27,6	27,6	27,6	27,6	.	27,6	27,6	27,6	27,6	27,6	19,6	22,9	23,4	23,4
(33) La Rochelle Niort sud	33,4	24,9	19,5	17,9	14,9	14,1	11,9	4,3	2,6	4,4	6,3	8,5	9,4	11,5	14,1	16,6	19,4	19,4	19,4	19,4	19,4	19,5	21,1	21,2	21,9	25	28,4	28,4	28,4	.	28,4	28,4	28,4	28,4	.	28,4	28,4	28,4	28,4	28,4	20,1	23,8	24	24	1,3
(34) St-Jean-d'Angély	38,1	29,6	24,2	22,6	19,6	18,8	16,6	9,3	7,1	10,5	11,3	13,9	14,4	17,5	20,3	21,5	23,8	23,8	23,8	23,8	23,8	24,2	27,1	27,2	27,6	30,2	33,9	33,9	33,9	.	33,9	33,9	33,9	33,9	.	33,9	33,9	33,9	33,9	33,9	25,3	28,7	30,1	30,1	5,5	4,2
(31) Rochefort ouest	.	.	.	.	.	.	.	.	.	.	.	.	.	.	.	.	.	.	.	.	.	.	.	.	.	.	.	.	.	.	.	.	.	.	.	.	.	.	.	.	.	.	.	.	.	.	.
(32) Rochefort nord	.	.	.	.	.	.	.	.	.	.	.	.	.	.	.	.	.	.	.	.	.	.	.	.	.	.	.	.	.	.	.	.	.	.	.	.	.	.	.	.	.	.	.	.	.	.	.	0
(33) Tonnay-Charente	.	.	.	.	.	.	.	.	.	.	.	.	.	.	.	.	.	.	.	.	.	.	.	.	.	.	.	.	.	.	.	.	.	.	.	.	.	.	.	.	.	.	.	.	.	.	.	1,2	1,2
(34) Tonnay-Charente	.	.	.	.	.	.	.	.	.	.	.	.	.	.	.	.	.	.	.	.	.	.	.	.	.	.	.	.	.	.	.	.	.	.	.	.	.	.	.	.	.	.	.	.	.	.	.	.	.	.
Péage de Cabariot	.	.	.	.	.	.	.	.	.	.	.	.	.	.	.	.	.	.	.	.	.	.	.	.	.	.	.	.	.	.	.	.	.	.	.	.	.	.	.	.	.	.	.	.	.	.	.	.	.	.	.
(35) Saintes	43,1	34,6	29,2	27,6	24,6	23,8	21,6	14,6	11,6	15,2	15,4	17,5	18,3	20,5	23,9	25,1	27	27	27	27	27	27,7	30,4	30,5	31,6	34,2	38	38	38	.	38	38	38	38	.	38	38	38	38	38	28,8	30,8	32,6	32,6	9,9	8,8	3,5	6,9	6,9	.	6,9	6,9
(36) Pons	46,5	38	32,6	31	28	27,2	25	17,6	15,5	18,9	19,5	20,6	21,4	23,8	27,5	28,3	30,4	30,4	30,4	30,4	30,4	30,4	33,9	34	34,4	37,2	41,5	41,5	41,5	.	41,5	41,5	41,5	41,5	.	41,5	41,5	41,5	41,5	41,5	32	34,3	36	36	13,6	13	6,1	11,1	11,1	.	11,1	11,1	2,6
(37) Mirambeau	50,4	41,9	36,5	34,9	31,9	31,1	28,9	21,5	20,3	23,5	24	24,3	24,9	27,2	30,5	31,6	33,1	33,1	33,1	33,1	33,1	33,6	36,7	36,8	37,3	40,5	44,4	44,4	44,4	.	44,4	44,4	44,4	44,4	.	44,4	44,4	44,4	44,4	44,4	35,2	37,6	39,7	39,7	17,9	16,8	10,3	16,1	16,1	.	16,1	16,1	6,1	2,8
(38) St-Aubin-de-Blaye	51,8	43,3	37,9	36,3	33,3	32,5	30,3	24	22,5	25,9	26,5	27,3	27,9	29	32,9	33,7	35	35	35	35	35	35,9	38,4	38,5	39,7	42,6	46,9	46,9	46,9	.	46,9	46,9	46,9	46,9	.	46,9	46,9	46,9	46,9	46,9	36,8	40,1	42,3	42,3	21,2	19,6	13,2	18,7	18,7	.	18,7	18,7	8,8	4,5	1,8
Péage de Virsac	53	44,5	39,1	37,5	34,5	33,7	31,5	30,6	30,5	34,8	35,2	36,2	36,9	37,8	40	42,6	43	43	43	43	43	44,8	47,2	47,3	48,1	51,5	53,7	53,7	53,7	.	53,7	53,7	53,7	53,7	.	53,7	53,7	53,7	53,7	53,7	45,1	47,5	50,2	50,2	29,2	28,7	21,6	27,3	27,3	.	27,3	27,3	17,9	13,5	9,4	6,5
(39) Libourne/St-Antoine	53	44,5	39,1	37,5	34,5	33,7	31,5	30,6	30,5	34,8	35,2	36,2	36,9	37,8	40	42,6	43	43	43	43	43	44,8	47,2	47,3	48,1	51,5	53,7	53,7	53,7	.	53,7	53,7	53,7	53,7	.	53,7	53,7	53,7	53,7	53,7	45,1	47,5	50,2	50,2	29,2	28,7	21,6	27,3	27,3	.	27,3	27,3	17,9	13,5	9,4	6,5	.
(40a) Blaye	.	.	.	.	.	.	.	.	.	.	.	.	.	.	.	.	.	.	.	.	.	.	.	.	.	.	.	.	.	.	.	.	.	.	.	.	.	.	.	.	.	.	.	.	.	.	.	.	.	.	.	.	.	.	.	.	.	0
(40b) St-André-de-Cubzac	.	.	.	.	.	.	.	.	.	.	.	.	.	.	.	.	.	.	.	.	.	.	.	.	.	.	.	.	.	.	.	.	.	.	.	.	.	.	.	.	.	.	.	.	.	.	.	.	.	.	.	.	.	.	.	.	.	0	.
(41) Ambes	53	44,5	39,1	37,5	34,5	33,7	31,5	30,6	30,5	34,8	35,2	36,2	36,9	37,8	40	42,6	43	43	43	43	43	44,8	47,2	47,3	48,1	51,5	53,7	53,7	53,7	.	53,7	53,7	53,7	53,7	.	53,7	53,7	53,7	53,7	53,7	45,1	47,5	50,2	50,2	29,2	28,7	21,6	27,3	27,3	.	27,3	27,3	17,9	13,5	9,4	6,5	.	0	0	0
(42) Ambarès/St-Loubès	53	44,5	39,1	37,5	34,5	33,7	31,5	30,6	30,5	34,8	35,2	36,2	36,9	37,8	40	42,6	43	43	43	43	43	44,8	47,2	47,3	48,1	51,5	53,7	53,7	53,7	.	53,7	53,7	53,7	53,7	.	53,7	53,7	53,7	53,7	53,7	45,1	47,5	50,2	50,2	29,2	28,7	21,6	27,3	27,3	.	27,3	27,3	17,9	13,5	9,4	6,5	.	0	0	0	0
(43) Sainte-Eulalie	53	44,5	39,1	37,5	34,5	33,7	31,5	30,6	30,5	34,8	35,2	36,2	36,9	37,8	40	42,6	43	43	43	43	43	44,8	47,2	47,3	48,1	51,5	53,7	53,7	53,7	.	53,7	53,7	53,7	53,7	.	53,7	53,7	53,7	53,7	53,7	45,1	47,5	50,2	50,2	29,2	28,7	21,6	27,3	27,3	.	27,3	27,3	17,9	13,5	9,4	6,5	.	0	0	0	0	0
(44) Carbon-Blanc	53	44,5	39,1	37,5	34,5	33,7	31,5	30,6	30,5	34,8	35,2	36,2	36,9	37,8	40	42,6	43	43	43	43	43	44,8	47,2	47,3	48,1	51,5	53,7	53,7	53,7	.	53,7	53,7	53,7	53,7	.	53,7	53,7	53,7	53,7	53,7	45,1	47,5	50,2	50,2	29,2	28,7	21,6	27,3	27,3	.	27,3	27,3	17,9	13,5	9,4	6,5	.	0	0	0	0	0	0
(45) Lormont	53	44,5	39,1	37,5	34,5	33,7	31,5	30,6	30,5	34,8	35,2	36,2	36,9	37,8	40	42,6	43	43	43	43	43	44,8	47,2	47,3	48,1	51,5	53,7	53,7	53,7	.	53,7	53,7	53,7	53,7	.	53,7	53,7	53,7	53,7	53,7	45,1	47,5	50,2	50,2	29,2	28,7	21,6	27,3	27,3	.	27,3	27,3	17,9	13,5	9,4	6,5	.	0	0	0	0	0	0	.

Bordeaux

CLASSE 2

Tarifs applicables au 1er février 2025

A11 A28 A81 A85

	Paris	Péage de St-Arnoult	1 Ablis	2 Chartres est	3 Thivars	4.1 Illiers-Combray	4 Luigny	5 La Ferté-Bernard	6 Connerré	7 Le Mans nord	23 Auvours	24 Parigné-l'Évêque	25 Écommoy	26 Montabon	Péage de St-Christophe	Péage du Roumois	13 Brionne	14 Bernay	15 Broglie ouest	16 Gacé	17 Sées	Péage d'Argentan	18 Alençon nord	19 Alençon sud	20 Rouessé-Fontaine	21 Maresché	8 Le Mans ouest	9 Le Mans sud	10 Sablé La Flèche	11 Durtal	12 Seiches-sur-le-Loir	Péage de Corzé	13 Pellouailles-les-Vignes	1 Joué-en-Charnie	2 Vaiges	3 Laval est	4 Laval ouest	Péage de La Gravelle	1 Beaufort-en-Vallée	2 Longué	3 Vivy Saumur	5 Bourgueil	Péage de Restigné	Angers
Péage de St-Arnoult	5,7																																											
1 Ablis	11,6	5																																										
2 Chartres est	13,5	7,2	3,1																																									
3 Thivars	17	10	5,5	2,4																																								
4.1 Illiers-Combray	20,4	12,4	8,1	4,8	2,6																																							
4 Luigny	24,6	17,6	13,8	9,5	6,7	4																																						
5 La Ferté-Bernard	30,6	22,8	18,4	13,6	11,1	8,3	3,9																																					
6 Connerré	32,8	25,1	20,4	18,4	13,2	10,6	7,9	4,8																																				
7 Le Mans nord	33,4	26,1	22,4	19,2	14,9	11,9	7,5	4,1	2,3																																			
23 Auvours	35,2	27,6	23,1	19,7	15,9	12,6	8,5	5,2	3,1	0,9																																		
24 Parigné-l'Évêque	37	29,9	26,2	23,1	18,9	15,6	11,5	7,2	4,8	2,8	2,4																																	
25 Écommoy	40,9	33,2	28,9	25,2	21,5	18	13,7	10,1	7,7	5,8	4,7	2,5																																
26 Montabon	49,1	42,3	37,2	34,5	30	26,5	23	18,2	17,4	14	13,2	10,6	7,6																															
Péage de St-Christophe	94,8	89,4	85,3	81,6	78,6	74,8	70,5	67	62,2	63,7	63,9	66	68,9	78,6																														
Péage du Roumois	80,9	75,5	71,4	67,7	64,7	60,9	56,6	53,1	48,3	49,8	50	52,1	55	64,7	4																													
13 Brionne	72,1	66,7	62,6	58,9	55,9	52,1	47,8	44,3	39,5	41	41,2	43,3	46,2	55,9	11,1	5,9																												
14 Bernay	65,6	60,2	56,1	52,4	49,4	45,6	41,3	37,8	33	34,5	34,7	36,8	39,7	49,4	18,1	9,4	3																											
15 Broglie ouest	57,4	52	47,9	44,2	41,2	37,4	33,1	29,6	24,8	26,3	26,5	28,6	31,5	41,2	26,1	15,9	9,5	5,9																										
16 Gacé	51,1	45,7	41,6	37,9	34,9	31,1	26,8	23,3	18,5	20	20,2	22,3	25,2	34,9	34,2	22,5	15,5	10,5	4,7																									
17 Sées	58,8	53,4	49,3	45,6	42,6	38,8	34,5	31	26,2	27,7	27,9	30	32,9	42,6	41,9	30,2	23,2	18,2	12,4	.																								
Péage d'Argentan	40	33,7	29,6	26,9	23,6	19,6	16	12,1	7,4	8,5	8,8	11,5	13,9	23,1	54,2	40,3	31,5	25	16,8	10,5	18,2																							
18 Alençon nord	38,8	32,8	28,9	26	22,6	18,8	14,8	11,3	6,4	7,8	8,1	10,5	11,9	21,9	55,3	41,4	32,6	26,1	17,9	11,6	19,3	1																						
19 Alençon sud	38,2	31,8	26,6	24,3	20,2	16,9	12,6	9,2	4,3	5,8	6,6	8,8	11,2	19,3	56,5	42,6	33,8	27,3	19,1	12,8	20,5	2,2	1																					
20 Rouessé-Fontaine	36,2	29,6	25,7	22,2	18,6	14,9	11,2	7,6	2,7	4,6	5,1	7,7	9,8	19,2	57,8	43,9	35,1	28,6	20,4	14,1	21,8	3,2	2,4	1,7																				
21 Maresché	35	26,9	23,1	19,6	16,5	13,5	8,1	6,9	2	4,2	4,8	6,9	9,5	17,9	63,7	49,8	41	34,5	26,3	20	27,7	9	7,9	6,2	4,9																			
8 Le Mans ouest	36,7	28,6	24,8	21,3	18,2	15,2	9,8	8,6	3,7	5,9	6,5	8,6	11,2	19,6	65,4	51,5	42,7	36,2	28	21,7	29,4	10,7	9,6	7,9	6,6	1,7																		
9 Le Mans sud	41	32,9	29,1	25,6	22,5	19,5	14,1	12,9	8	10,2	10,8	12,9	15,5	23,9	69,7	55,8	47	40,5	32,3	26	33,7	15	13,9	12,2	10,9	6	5,1																	
10 Sablé La Flèche	42,9	34,8	31	27,5	24,4	21,4	16	14,8	9,9	12,1	12,7	14,8	17,4	25,8	71,6	57,7	48,9	42,4	34,2	27,9	35,6	16,9	15,8	14,1	12,8	7,9	7	1,8																
11 Durtal	46,6	38,5	34,7	31,2	28,1	25,1	19,7	18,5	13,6	15,8	16,4	18,5	21,1	29,5	75,3	61,4	52,6	46,1	37,9	31,6	39,3	20,6	19,5	17,8	16,5	11,6	9,7	3,8	1,8															
12 Seiches-sur-le-Loir	50,4	42,3	38,5	35	31,9	28,9	23,5	22,3	17,4	19,6	20,2	22,3	24,9	33,3	79,1	65,2	56,4	49,9	41,7	35,4	43,1	24,4	23,3	21,6	20,3	15,4	14,6	7,7	5,6	3,3														
Péage de Corzé	50,4	42,3	38,5	35	31,9	28,9	23,5	22,3	17,4	19,6	20,2	22,3	24,9	33,3	79,1	65,2	56,4	49,9	41,7	35,4	43,1	24,4	23,3	21,6	20,3	15,4	14,6	7,7	5,6	3,3	.													
13 Pellouailles-les-Vignes	40	33,1	28,4	25,8	22,1	19,2	13,4	11	6	8,5	9,6	11,8	15	23,1	67,2	53,3	44,5	38	29,8	23,5	31,2	12,7	12,4	9,6	8,8	5,7	7,4	11,7	13,6	17,3	21,1	21,1												
1 Joué-en-Charnie	44,1	37,4	33,3	30,2	26,6	23	18,1	15,4	10,5	12,1	13	16,1	18,6	28	72,2	58,3	49,5	43	34,8	28,5	36,2	17,2	16,2	14,2	13,1	9,1	10,8	15,1	17	20,7	24,5	24,5	2,3											
2 Vaiges	47,1	40,4	36,3	33,2	29,6	26	21,1	18,4	13,5	15,1	16,4	19,1	21,6	31	74,5	60,6	51,8	45,3	37,1	30,8	38,5	20,2	19,2	17,3	16,4	12,4	14,1	18,4	20,3	24	27,8	27,8	5,3	3,2										
3 Laval est	48,2	42,1	37,7	34,5	31,5	27,8	23	20,4	15,5	17,3	18,3	20,5	23,9	31,6	76	62,1	53,3	46,8	38,6	32,3	40	21,7	20,5	18,8	18	14,7	16,4	20,7	22,6	26,3	30,1	30,1	6,8	4,1	1,4									
4 Laval ouest	50,1	45	42,5	38,5	36,2	32,5	26,7	24,7	20,2	22,6	22,9	26,2	28,7	33,2	79,3	65,4	56,6	50,1	41,9	35,6	43,3	25	24,1	23,2	22,6	18,5	20,2	24,5	26,4	30,1	33,9	33,9	11,3	8	5,2	4,1								
Péage de La Gravelle	50,1	42	38,2	34,7	31,6	28,6	23,2	22	17,1	19,3	19,9	22	24,6	33	78,8	64,9	56,1	49,6	41,4	35,1	42,8	24,1	23	21,3	20	15,1	13	7,6	5,4	3,3	6,3	6,3	20,8	24,2	27,5	29,8	33,6								
1 Beaufort-en-Vallée	51,3	43,2	39,4	35,9	32,8	29,8	24,4	23,2	18,3	20,5	21,1	23,2	25,8	34,2	80	66,1	57,3	50,8	42,6	36,3	44	25,3	24,2	22,5	21,2	16,3	14,2	8,8	6,6	4,5	7,5	7,5	22	25,4	28,7	31	34,8	1,1							
2 Longué	53,8	45,7	41,9	38,4	35,3	32,3	26,9	25,7	20,8	23	23,6	25,7	28,3	36,7	82,5	68,6	59,8	53,3	45,1	38,8	46,5	27,8	26,7	25	23,7	18,8	16,7	11,3	9,1	7	10	10	24,5	27,9	31,2	33,5	37,3	2,3	2,1						
3 Vivy Saumur	56,2	48,1	44,3	40,8	37,7	34,7	29,3	28,1	23,2	25,4	26	28,1	30,7	39,1	84,9	71	62,2	55,7	47,5	41,2	48,9	30,2	29,1	27,4	26,1	21,2	19,1	13,7	11,5	9,4	12,4	12,4	26,9	30,3	33,6	35,9	39,7	4,6	3,4	2,7				
5 Bourgueil	62,1	54	50,2	46,7	43,6	40,6	35,2	34	29,1	31,3	31,9	34	36,6	45	90,8	76,9	68,1	61,6	53,4	47,1	54,8	36,1	35	33,3	32	27,1	25	19,6	17,4	15,3	18,3	18,3	32,8	36,2	39,5	41,8	45,6	9,1	8,3	8,2	4,3			

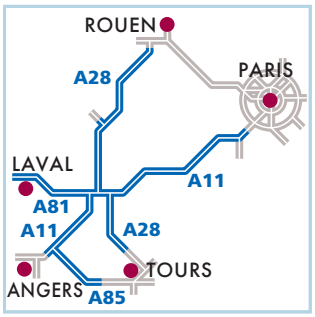

Le prix du péage peut inclure le prix du péage des trajets d'autres sociétés d'autoroutes au nom et pour le compte desquelles agit la société Autoroutes du Sud de la France percevant le péage en sortie.

CLASSE 2

Tarifs applicables au 1er février 2025

A72 A89

	9 La Fouillouse	8 Andrézieux-Bouthéon sud	8 Andrézieux-Bouthéon nord	Péage de Veauchette	7 Montbrison Montrond	6 Feurs	Tour de Salvagny limite de concession	38 Lentilly	37 Pont de Dorieux	36 L'Arbresle	35 Tarare est (péage en système ouvert)	Péage de St-Romain-de-Popey	35 Tarare est (péage en système fermé)	34 Tarare ouest	33 Balbigny	32 St-Germain-Laval	31 Noirétable	30 Thiers est	29 Thiers ouest	28 Lezoux	Péage des Martres-d'Artière	Clermont-Ferrand limite de concession	1.6 Pont du Château
0																							
.	.																						
.	.	.																					
1,7	.	1,7	1,7																				
4	.	4	4	1,6																			
18	.	18	18	15,1	12,8																		
18	.	18	18	15,1	12,8	0																	
18	.	18	18	15,1	12,8	0	0																
18	.	18	18	15,1	12,8	0	0	0															
.	.	.	.	.	.	2,8	2,8	2,8	2,8														
18	.	18	18	15,1	12,8	.	.	.	.	.													
12,9	.	12,9	12,9	10,2	8,3					.	.												
11,7	.	11,7	11,7	8,9	6,3	4,7	4,7	4,7	4,7	.	4,7	1,2											
7,1	.	7,1	7,1	4,3	2,1	9	9	9	9	.	9	5,6	3,9										
6,1	.	6,1	6,1	3,9	2,3	12,3	12,3	12,3	12,3	.	12,3	7,8	6,2	1,5									
9,7	.	9,7	9,7	7,5	5,7	16	16	16	16	.	16	11,5	10,5	5,3	2,8								
12	.	12	12	11,3	8,1	19,4	19,4	19,4	19,4	.	19,4	14	12,9	7,7	5,2	2							
14,5	.	14,5	14,5	13	11,1	22,2	22,2	22,2	22,2	.	22,2	17	16	10,4	7,8	4,3	1,6						
15,4	.	15,4	15,4	13,9	11,9	22,7	22,7	22,7	22,7	.	22,7	17,4	16,4	11,7	9,2	5,6	2,9	1,3					
17,2	.	17,2	17,2	17	16,8	25,2	25,2	25,2	25,2	.	25,2	22	21,3	16,2	13,5	9,5	6,1	4,5	3,3				
17,2	.	17,2	17,2	17	16,8	25,2	25,2	25,2	25,2	.	25,2	22	21,3	16,2	13,5	9,5	6,1	4,5	3,3	.			
17,2	.	17,2	17,2	17	16,8	25,2	25,2	25,2	25,2	.	25,2	22	21,3	16,2	13,5	9,5	6,1	4,5	3,3	.	.		

St-Étienne — A72 — A89 — A711 — Clermont-Ferrand

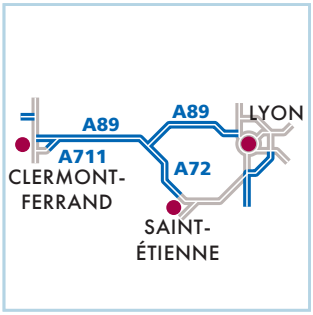

A89 A10 A19 A6 A71 A5 A26 A4 A31 A36 A39 A40 A52

	27 Manzat	26 Vulcania Bromont	25 St-Julien Sancy	24 Ussel est	23 Ussel ouest	22 Egletons	21 Tulle est	20 Tulle nord	Péage de St-Germain-les-Vergnes
3,1									
6,9	3,6								
11,1	8,5	4,3							
13,6	10,8	7,2	2,5						
18	14,3	11,5	6,6	4					
21,5	18,2	16,4	9,5	7,8	2,7				
23,1	18,8	17,3	10,5	8,9	4,1	1			
27,2	24,1	22,1	14,9	12,7	7,6	3,5	2,3		
27,2	24,1	22,1	14,9	12,7	7,6	3,5	2,3	.	

Clermont-Ferrand — A89 — St Germain les Vergnes — Brive

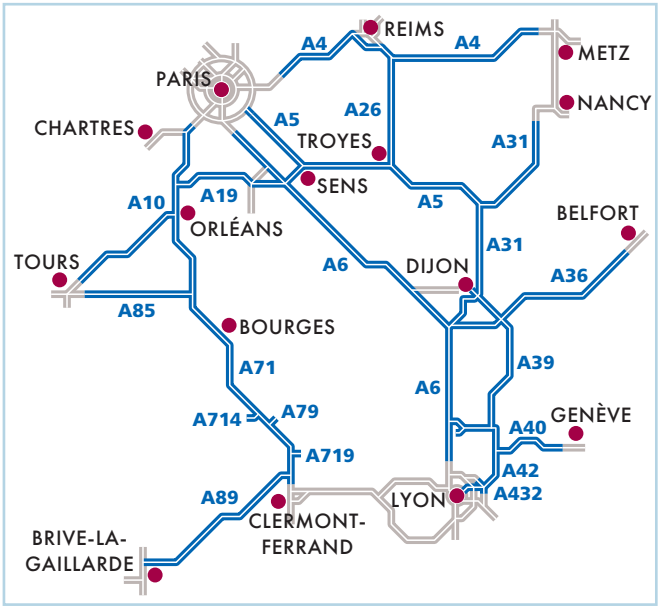

Péage de Clermont	14 Gerzat	13 Riom	12.1 Combronde	Péage de Gannat A719	11 Montmarault	Péage de Deux Chaises A79	Péage de Montluçon A714	9 Forêt de Tronçais	8 St-Amand-Montrond	7 Bourges	6 Vierzon est	5 Vierzon nord	14 Villefranche-sur-Cher	13 Chémery	12 St-Romain-sur-Cher	11 Bléré	10 Esvres	Péage de Veigné	4 Salbris	3 Lamotte-Beuvron	2 Olivet	1 Orléans centre	Péage de St-Arnoult	11 Allainville	12 Allaines	13 Artenay	13.1 Gidy	14 Orléans nord	15 Meung-sur-Loire	16 Mer	17 Blois	18 Amboise/Château-Renault	Péage de Monnaie	
33,9	31,2	29,8	25,2	20,5	18,3	13,8	9,5	6,2																										
31,9	29,2	27,8	23,2	18,5	16,3	11,8	7,5	4,2																										
31	28,3	26,9	22,3	17,6	15,4	10,9	6,6	3,3																										
29,9	27,2	25,8	21,2	16,5	14,3	9,8	5,5	2,2																										
33,1	30,4	29	24,4	19,7	17,5	13	8,7	5,4																										
36,2	33,5	32,1	27,5	22,8	20,6	16,1	11,8	8,5																										
36,8	34,1	32,7	28,1	23,4	21,2	16,7	12,4	9,1																										
40,4	37,7	36,3	31,7	27	24,8	20,3	16	12,7																										
40,6	37,9	36,5	31,9	27,2	25	20,5	16,2	12,9																										
44,8	42,1	40,7	36,1	31,4	29,2	24,7	20,4	17,1																										
51,9	49,2	47,8	43,2	38,5	36,3	31,8	27,5	24,2																										
56,9	54,2	52,8	48,2	43,5	41,3	36,8	32,5	29,2																										
57,1	54,4	53	48,4	43,7	41,5	37	32,7	29,4																										
62,9	60,2	58,8	54,2	49,5	47,3	42,8	38,5	35,2																										
65,5	62,8	61,4	56,8	52,1	49,9	45,4	41,1	37,8																										
68,6	65,9	64,5	59,9	55,2	53	48,5	44,2	40,9																										
74,2	71,5	70,1	65,5	60,8	58,6	54,1	49,8	46,5																										
77,4	74,7	73,3	68,7	64	61,8	57,3	53	49,7																										
79,3	76,6	75,2	70,6	65,9	63,7	59,2	54,9	51,6																										
60,9	58,2	56,8	52,2	47,5	45,3	40,8	36,5	33,2																										
63,6	60,9	59,5	54,9	50,2	48	43,5	39,2	35,9																										
70,1	67,4	66	61,4	56,7	54,5	50	45,7	42,4																										
71,7	69	67,6	63	58,3	56,1	51,6	47,3	44																										
90,8	88,1	86,7	82,1	77,4	75,2	70,7	66,4	63,1																										
86,5	83,8	82,4	77,8	73,1	70,9	66,4	62,1	58,8																										
80,8	78,1	76,7	72,1	67,4	65,2	60,7	56,4	53,1																										
77,7	75	73,6	69	64,3	62,1	57,6	53,3	50																										
74,2	71,5	70,1	65,5	60,8	58,6	54,1	49,8	46,5																										
73,3	70,6	69,2	64,6	59,9	57,7	53,2	48,9	45,6																										
76,1	73,4	72	67,4	62,7	60,5	56	51,7	48,4																										
79,5	76,8	75,4	70,8	66,1	63,9	59,4	55,1	51,8																										
81,8	79,1	77,7	73,1	68,4	66,2	61,7	57,4	54,1																										
86,2	83,5	82,1	77,5	72,8	70,6	66,1	61,8	58,5																										
93,9	91,2	89,8	85,2	80,5	78,3	73,8	69,5	66,2																										

A71 — A85 — A71 — A10

CLASSE 2

Tarifs applicables au 1er février 2025

A89 A10 A19 A6 A71 A5 A26 A4 A31 A36 A39 A40 A42

Péage de St-Germain-les-Vergnes	(20) Tulle nord	(21) Tulle est	(22) Egletons	(23) Ussel ouest	(24) Ussel est	(25) St-Julien Sancy	(26) Vulcania Bromont	(27) Manzat		
84,2	81,5	80,1	75,5	70,8	68,6	64,1	59,8	56,5	(8) Escrennes	A19
90,1	87,4	86	81,4	76,7	74,5	70	65,7	62,4	(7) Auxy	A19
94,6	91,9	90,5	85,9	81,2	79	74,5	70,2	66,9	(6) Gondreville nord	A19
101,3	98,6	97,2	92,6	87,9	85,7	81,2	76,9	73,6	(6) Gondreville sud	A19
97,4	94,7	93,3	88,7	84	81,8	77,3	73	69,7	(5) Fontenay-sur-Loing	A19
103,6	100,9	99,5	94,9	90,2	88	83,5	79,2	75,9	(4) St-Hilaire-les-Andrésis	A19
103,9	101,2	99,8	95,2	90,5	88,3	83,8	79,5	76,2	(3) Savigny-sur-Clairis	A19
111,3	108,6	107,2	102,6	97,9	95,7	91,2	86,9	83,6	(2) Villeneuve-Dondagre	A19
113,3	110,6	109,2	104,6	99,9	97,7	93,2	88,9	85,6	(1) St-Denis-les-Sens	A19
119,5	116,8	115,4	110,8	106,1	103,9	99,4	95,1	91,8	Péage de Fleury-en-Bière	A6
116,2	113,5	112,1	107,5	102,8	100,6	96,1	91,8	88,5	(14) Ury	A6
115,1	112,4	111	106,4	101,7	99,5	95	90,7	87,4	(15) Fontainebleau	A6
115,1	112,4	111	106,4	101,7	99,5	95	90,7	87,4	(16) Nemours	A6
109,5	106,8	105,4	100,8	96,1	93,9	89,4	85,1	81,8	(17) Courtenay	A6
111,9	109,2	107,8	103,2	98,5	96,3	91,8	87,5	84,2	(18) Joigny	A6
116,4	113,7	112,3	107,7	103	100,8	96,3	92	88,7	(19) Auxerre nord	A6
116,4	113,7	112,3	107,7	103	100,8	96,3	92	88,7	(20) Auxerre sud	A6
119,9	117,2	115,8	111,2	106,5	104,3	99,8	95,5	92,2	(21) Nitry	A6
123	120,3	118,9	114,3	109,6	107,4	102,9	98,6	95,3	(22) Avallon	A6
125,8	123,1	121,7	117,1	112,4	110,2	105,7	101,4	98,1	(23) Bierre-les-Semur	A6
132,1	129,4	128	123,4	118,7	116,5	112	107,7	104,4	Péage de Pouilly-en-Auxois	A6
136,6	133,9	132,5	127,9	123,2	121	116,5	112,2	108,9	(24) Beaune nord	A6
138,1	135,4	134	129,4	124,7	122,5	118	113,7	110,4	(24.1) Beaune sud	A6
142,2	139,5	138,1	133,5	128,8	126,6	122,1	117,8	114,5	(25.1) Chalon nord	A6
142,2	139,5	138,1	133,5	128,8	126,6	122,1	117,8	114,5	(25.2) Chalon centre	A6
142,2	139,5	138,1	133,5	128,8	126,6	122,1	117,8	114,5	(26) Chalon sud	A6
144,7	142	140,6	136	131,3	129,1	124,6	120,3	117	(27) Tournus	A6
149,1	146,4	145	140,4	135,7	133,5	129	124,7	121,4	(28) Mâcon nord	A6
150,5	147,8	146,4	141,8	137,1	134,9	130,4	126,1	122,8	(29) Mâcon sud	A6
152,9	150,2	148,8	144,2	139,5	137,3	132,8	128,5	125,2	(30) Belleville-sur-Saône	A6
153,8	151,1	149,7	145,1	140,4	138,2	133,7	129,4	126,1	(31.1) Villefranche nord	A6
155,4	152,7	151,3	146,7	142	139,8	135,3	131	127,7	(31.2) Villefranche ville	A6
160,4	157,7	156,3	151,7	147	144,8	140,3	136	132,7	Péage de Villefranche-Limas	A6
117,8	115,1	113,7	109,1	104,4	102,2	97,7	93,4	90,1	(17) Val de Loing/Souppes	A77
127,6	124,9	123,5	118,9	114,2	112	107,5	103,2	99,9	Péage de Val de Loing barrière	A77
123,8	121,1	119,7	115,1	110,4	108,2	103,7	99,4	96,1	Péage des Eprunes	A5
121,6	118,9	117,5	112,9	108,2	106	101,5	97,2	93,9	(15) St-Germain-Laxis	A5
121,6	118,9	117,5	112,9	108,2	106	101,5	97,2	93,9	(16) Chatillon-Laborde	A5
117,3	114,6	113,2	108,6	103,9	101,7	97,2	92,9	89,6	(17) Forges	A5
117,3	114,6	113,2	108,6	103,9	101,7	97,2	92,9	89,6	(18) Marolles-sur-Seine	A5
117,3	114,6	113,2	108,6	103,9	101,7	97,2	92,9	89,6	(19) Vulaines	A5
121,6	118,9	117,5	112,9	108,2	106	101,5	97,2	93,9	(20) Torvilliers	A5
122,4	119,7	118,3	113,7	109	106,8	102,3	98	94,7	(21) St-Thibault	A5
126,3	123,6	122,2	117,6	112,9	110,7	106,2	101,9	98,6	(22) Magnant	A5
129,1	126,4	125	120,4	115,7	113,5	109	104,7	101,4	(23) Ville-sous-la-Ferté	A5
131,8	129,1	127,7	123,1	118,4	116,2	111,7	107,4	104,1	(24) Chaumont/Semoutiers	A5
124,6	121,9	120,5	115,9	111,2	109	104,5	100,2	96,9	(23) Thennelières	A26
127,9	125,2	123,8	119,2	114,5	112,3	107,8	103,5	100,2	(22) Charmont-sous-Barbuise	A26
130	127,3	125,9	121,3	116,6	114,4	109,9	105,6	102,3	(21) Vallée de l'Aube	A26
133,3	130,6	129,2	124,6	119,9	117,7	113,2	108,9	105,6	(20) Sommesous	A26
134	131,3	129,9	125,3	120,6	118,4	113,9	109,6	106,3	(19) Vatry	A26
136,7	134	132,6	128	123,3	121,1	116,6	112,3	109	(18) Mont-Choisy	A26
138	135,3	133,9	129,3	124,6	122,4	117,9	113,6	110,3	(17) St-Gibrien	A26
144,9	142,2	140,8	136,2	131,5	129,3	124,8	120,5	117,2	Péage de Reims est	A4
144,3	141,6	140,2	135,6	130,9	128,7	124,2	119,9	116,6	(23) Reims sud	A4
146,6	143,9	142,5	137,9	133,2	131	126,5	122,2	118,9	Péage Reims nord A26	A4
147,4	144,7	143,3	138,7	134	131,8	127,3	123	119,7	(22) Reims ouest	A4
148,9	146,2	144,8	140,2	135,5	133,3	128,8	124,5	121,2	(21) Dormans	A4
152,5	149,8	148,4	143,8	139,1	136,9	132,4	128,1	124,8	(20) Château-Thierry	A4
156	153,3	151,9	147,3	142,6	140,4	135,9	131,6	128,3	(19) Montreuil-Reims	A4
159,4	156,7	155,3	150,7	146	143,8	139,3	135	131,7	Péage de Montreuil-aux-Lions	A4
139,6	136,9	135,5	130,9	126,2	124	119,5	115,2	111,9	(27) Châlons/La Veuve	A4

Péage de St-Germain-les-Vergnes	(20) Tulle nord	(21) Tulle est	(22) Egletons	(23) Ussel ouest	(24) Ussel est	(25) St-Julien Sancy	(26) Vulcania Bromont	(27) Manzat		
139,9	137,2	135,8	131,2	126,5	124,3	119,8	115,5	112,2	(27) Châlons/Mourmelon	A4
139,9	137,2	135,8	131,2	126,5	124,3	119,8	115,5	112,2	(28) St-Etienne-au-Temple	A4
143,7	141	139,6	135	130,3	128,1	123,6	119,3	116	(29) Ste-Menehould	A4
146,3	143,6	142,2	137,6	132,9	130,7	126,2	121,9	118,6	(29.1) Clermont-en-Argonne	A4
149,7	147	145,6	141	136,3	134,1	129,6	125,3	122	(30) Voie Sacrée	A4
153,7	151	149,6	145	140,3	138,1	133,6	129,3	126	(31) Verdun	A4
153,7	151	149,6	145	140,3	138,1	133,6	129,3	126	(32) Fresnes-en-Woevre	A4
156,6	153,9	152,5	147,9	143,2	141	136,5	132,2	128,9	(33) Jarny	A4
160,7	158	156,6	152	147,3	145,1	140,6	136,3	133	Péage de Beaumont	A4
150,6	147,9	146,5	141,9	137,2	135	130,5	126,2	122,9	Péage de Gye	A31
147,4	144,7	143,3	138,7	134	131,8	127,3	123	119,7	(11) Colombey-les-Belles	A31
143,5	140,8	139,4	134,8	130,1	127,9	123,4	119,1	115,8	(10) Chatenois sud	A31
142,8	140,1	138,7	134,1	129,4	127,2	122,7	118,4	115,1	(9) Bulgneville	A31
140,6	137,9	136,5	131,9	127,2	125	120,5	116,2	112,9	(8.1) Robecourt	A31
137	134,3	132,9	128,3	123,6	121,4	116,9	112,6	109,3	(8) Montigny-le-Roi	A31
134,5	131,8	130,4	125,8	121,1	118,9	114,4	110,1	106,8	(7) Langres nord	A31
135,9	133,2	131,8	127,2	122,5	120,3	115,8	111,5	108,2	(6) Langres sud	A31
139,4	136,7	135,3	130,7	126	123,8	119,3	115	111,7	(5) Til-Chatel	A31
145	142,3	140,9	136,3	131,6	129,4	124,9	120,6	117,3	(4) Dijon/Arc-sur- Tille	A31
142,6	139,9	138,5	133,9	129,2	127	122,5	118,2	114,9	Péage de Dijon sud A311	A31
139,7	137	135,6	131	126,3	124,1	119,6	115,3	112	(1) Nuits-St-Georges	A31
141,8	139,1	137,7	133,1	128,4	126,2	121,7	117,4	114,1	(1) Seurre	A36
145,5	142,8	141,4	136,8	132,1	129,9	125,4	121,1	117,8	(2) Dôle	A36
147,4	144,7	143,3	138,7	134	131,8	127,3	123	119,7	(2.1) Gendrey	A36
150,7	148	146,6	142	137,3	135,1	130,6	126,3	123	(3) Besançon ouest	A36
151,3	148,6	147,2	142,6	137,9	135,7	131,2	126,9	123,6	(4) Besançon nord	A36
152,4	149,7	148,3	143,7	139	136,8	132,3	128	124,7	(4.1) Besançon est	A36
156	153,3	151,9	147,3	142,6	140,4	135,9	131,6	128,3	(5) Baume-les-Dames	A36
158,3	155,6	154,2	149,6	144,9	142,7	138,2	133,9	130,6	(6) L'Isle-sur-le-Doubs	A36
165,5	162,8	161,4	156,8	152,1	149,9	145,4	141,1	137,8	Péage de St-Maurice	A36
143,2	140,5	139,1	134,5	129,8	127,6	123,1	118,8	115,5	Péage de Dijon/Crimolois	A39
143,5	140,8	139,4	134,8	130,1	127,9	123,4	119,1	115,8	(5) Soirans	A39
145,5	142,8	141,4	136,8	132,1	129,9	125,4	121,1	117,8	(6) Choisey	A39
149,9	147,2	145,8	141,2	136,5	134,3	129,8	125,5	122,2	Péage de Bersaillin A391	A39
151,3	148,6	147,2	142,6	137,9	135,7	131,2	126,9	123,6	(7.1) Arlay	A39
153	150,3	148,9	144,3	139,6	137,4	132,9	128,6	125,3	(8) Beaurepaire	A39
154,5	151,8	150,4	145,8	141,1	138,9	134,4	130,1	126,8	(9) Le Miroir	A39
156,5	153,8	152,4	147,8	143,1	140,9	136,4	132,1	128,8	(10) Beaupont	A39
158,8	156,1	154,7	150,1	145,4	143,2	138,7	134,4	131,1	Péage de Val de Saône A406	A40
149,5	146,8	145,4	140,8	136,1	133,9	129,4	125,1	121,8	(1) Mâcon centre	A40
149,8	147,1	145,7	141,1	136,4	134,2	129,7	125,4	122,1	(2) Feillens	A40
149,8	147,1	145,7	141,1	136,4	134,2	129,7	125,4	122,1	(3) Replonges	A40
156,2	153,5	152,1	147,5	142,8	140,6	136,1	131,8	128,5	(4) St-Genis	A40
153,4	150,7	149,3	144,7	140	137,8	133,3	129	125,7	(5) Bourg nord	A40
153,5	150,8	149,4	144,8	140,1	137,9	133,4	129,1	125,8	(6) Viriat	A40
155,7	153	151,6	147	142,3	140,1	135,6	131,3	128	(7) Bourg sud	A40
163,3	160,6	159,2	154,6	149,9	147,7	143,2	138,9	135,6	(8) St-Martin-du-Fresne	A40
164,3	161,6	160,2	155,6	150,9	148,7	144,2	139,9	136,6	(9) Sylans sud	A40
171,1	168,4	167	162,4	157,7	155,5	151	146,7	143,4	(10) Bellegarde	A40
173,6	170,9	169,5	164,9	160,2	158	153,5	149,2	145,9	(11) Eloise	A40
181,1	178,4	177	172,4	167,7	165,5	161	156,7	153,4	Péage de Viry	A40
163,4	160,7	159,3	154,7	150	147,8	143,3	139	135,7	(9) La Croix-Chalon	A404
166,2	163,5	162,1	157,5	152,8	150,6	146,1	141,8	138,5	Péage de Groissiat	A404
158,1	155,4	154	149,4	144,7	142,5	138	133,7	130,4	(9) Pont-d'Ain	A42
159,5	156,8	155,4	150,8	146,1	143,9	139,4	135,1	131,8	(8) Ambérieu	A42
161,5	158,8	157,4	152,8	148,1	145,9	141,4	137,1	133,8	(7) Pérouges	A42
161,5	158,8	157,4	152,8	148,1	145,9	141,4	137,1	133,8	(6) Balan	A42
163,6	160,9	159,5	154,9	150,2	148	143,5	139,2	135,9	(5.1) La Boise/Montuel	A42
165,6	162,9	161,5	156,9	152,2	150	145,5	141,2	137,9	Péage de Beynost	A42
164,8	162,1	160,7	156,1	151,4	149,2	144,7	140,4	137,1	Péage de La Côtière	A432
167,9	165,2	163,8	159,2	154,5	152,3	147,8	143,5	140,2	Péage de La Boisse	A432

Le prix du péage peut inclure le prix du péage des trajets d'autres sociétés d'autoroutes au nom et pour le compte desquelles agit la société Autoroutes du Sud de la France percevant le péage en sortie.